מינהל התכנון
חוק התכנון והבניה, התשכ"ה - 1965
מחוז ירושלים
הוועדה המחוזית החליטה ביום :
30/10/2023
להפקיד את התכנית
14/10/2026
תאריך יו"ר הוועדה המחוזית
תכנית 101-1095330 נספח סקר קרקע היסטורי 11:17:12 20/01/2026 נספח סקר קרקע היסטורי

לשם שפר
איכות סביבה בע"מ

תכנית מס' 101-1095330

מתחם רג'ואן- הסדנא- פייר קניג, ירושלים

סקר היסטורי Phase 1

ירושלים – ינואר 2023

לשם שפר איכות סביבה בע"מ, רח' הנטקה 34, ת.ד. 3694, ירושלים 91036, טלפון 02-6427684, פקס. 02-6427103, דוא"ל shl@shl.co.il

תכנית 101-1095330 20/01/2026 11:17:12 נספח סקר קרקע היסטורי נספח קרקע היסטורי

מתחם רג'ואן – הסדנה – פייר קניג - ירושלים (תכנית מס' 101-1095330)

סקר היסטורי Phase 1

הסקר הוכן ע"י: לשם - שפר איכות סביבה בע"מ
עבור: רג'ואן אחזקות

עורכי הסקר: ד"ר מוקי שפר ויונתן תורג'מן.
גרפיקה: נינה ארונוביץ.

לשם שפר איכות סביבה בע"מ, רח' הנטקה 34, ת.ד. 3694, ירושלים 91036, טלפון 02-6427684, פקס. 02-6427103, דוא"ל shl@shl.co.il

תכנית 101-1095330 20/01/2026 11:17:12 נספח סקר קרקע היסטורי נספח קרקע היסטורי

תוכן העניינים

תוכן העניינים *3*
תקציר *4*
מבוא ורקע *5*
סקר היסטורי *6*
1.1 סיורים באתר וסביבתו 6
1.2 שם האתר / מפעל 6
1.3 מיקום האתר: 6
1.4 שימושי קרקע וייעודי קרקע 7
1.5 תצ"אות וצילומים 7
1.6 מידע קרטוגרפי 8
1.7 מידע על הנכס 8
1.8 פירוט הפעילות באתר 8
1.9 פירוט של התשתיות והתכסית באתר 9
1.10 מידע הידרו-גיאולוגי 9
1.11 מידע על היסטוריה של זיהומים ומיפוי המידע באתר וסביבתו 10
1.12 ניתוח ופרשנות הממצאים 18
1.13 פירוט מקורות מידע לסקר זה 22

תקציר

נספח זה הנו סקר היסטורי מס' 101-1095330 מתחם רג'ואן- הסדנא- פייר קניג, ירושלים.
התכנית מציעה הריסת 3 מבנים קיימים ובניית 3 מבני מגורים עד 30 קומות ע"ג מסד של מסחר ותעסוקה, זאת בנוסף לבניית מבנה ציבור עד לגובה של 5 קומות.

שטח התכנית משמש ל- 3 מבני מלאכה הכוללים יחידות רבות. 2 מבנים בני 2 קומות, ומבנה אחד בן 6 קומות.
היחידות אינן בבעלות אחת, אלא הוחכרו לבעלי מלאכה שונים ל- 9,999 שנים.
אותרו בשטח התכנית מספר מוסכים קיימים והיסטוריים, בתי דפוס קיימים והיסטוריים וכן מחסן מצברים.

הסקר ההיסטורי כולל הצעה לתכנית דיגום קרקע אשר כוללת 51 נקודות דיגום בהתאם לשימושים השונים.

לשם שפר איכות סביבה בע"מ, רח' הנטקה 34, ת.ד. 3694, ירושלים 91036, טלפון 02-6427684, פקס. 02-6427103, דוא"ל shl@shl.co.il

מבוא ורקע

נספח זה הנו סקר היסטורי לתכנית מס' 101-1095330 מתחם רג'ואן- הסדנא- פייר קניג, ירושלים

תכנית מס' 101-1095330 ממוקמת ברחוב הסדנא 7-5, בפינת פייר קניג, בשכונת תלפיות, ירושלים.
מטרת התכנית שינוי הייעוד מתעשייה למגורים, מסחר ותעסוקה וכן הגדלת זכויות הבניה בהתאם לתכנית האב.
כחלק מהליכי אישור התכנית, עלתה הדרישה לבחון האם קיים פוטנציאל מהותי לקיומו של זיהום קרקע בשטח המתחם. לצורך הבחינה היה צורך לבצע במקום סקר קרקע היסטורי לבחינת קיומם ואיתורם של מקורות פוטנציאליים לזיהום היסטורי של הקרקע.

הסקר ההיסטורי המוצג להלן, מציג את תמונת המצב בשטח ואת הפעילויות ההיסטוריות, תוך ניתוח האפשרות לקיומו של זיהום קרקע בשטח המתחם והוא כולל ממצאים ומסקנות.

סקר היסטורי

1.1 סיורים באתר וסביבתו

סיור נערך באתר– בתאריך 9/11/2022 בליווי מר אבי רלבג, אחראי קשר עם בעלי הנכסים מטעם רג'ואן+ ראיון מקיף עמו.
בסיור הייתה גישה לכל המתחם. בנוסף, ככל הניתן בוצעו ראיונות עם בעלי ומחזיקי היחידות.
נערך עיון בארכיון עיריית ירושלים.

1.2 שם האתר / מפעל

התכנית מציעה הריסת 3 מבני תעשייה ומסחר קיימים ובניית 3 מבני מגורים עד 30 קומות ע"ג מסד של מסחר ותעסוקה זאת בנוסף לבניית מבנה ציבור עד לגובה של 5 קומות.

1.3 מיקום האתר:

התכנית ממוקמת בפינת הרחובות הסדנא, יד חרוצים, בירושלים.

מיקום התכנית בסביבה מוצג בתרשים מס' 1.
תצלום אוויר של אזור התכנית, הכולל את שימושי הקרקע, מוצג בתרשים מס' 2.
נ.צ. של האתר : 220391/628562
גוש 30140 חלקה 8.
שטח האתר : 13.33 דונם.
שטח האתר הנסקר: כ 20 דונם
שנת הקמת המפעל / נכס: המבנים נבנו ע"י חברת אמינפא – בשנות ה – 70.
סוג נכס: מבנה תעשייה, בעלים מרובים.
בעלים נוכחיים: אמינפא הנה חברה משכנת, המבנה נבנה על ידם, כאשר היחידות נמכרו לבעלי מלאכה ועסקים (אלו לא שוכרים אלא חוכרים ל- 9999 שנים, בפועל - בעלים). נסחי טאבו קיימים אצלי, אך עקב גודל הקובץ (131 עמודים אשר לטעמי יסרבלו את הקריאה של מסמך זה) – לא צורפו, במידת הצורך הנסח המלא יועבר בנפרד ולפי דרישה.
בעלים היסטוריים: שטח התכנית נרכש ע"י חברת אמינפא בשנת 1979. לא אותרו רישומים קודמים.

תכנית 101-1095330 נספח סקר קרקע היסטורי נספח סקר קרקע היסטורי 20/01/2026 11:17:12

תרשים מס' 1
מיקום התכנית וסביבתה
קנ"מ 1:10,000

מקרא:

גבול התכנית

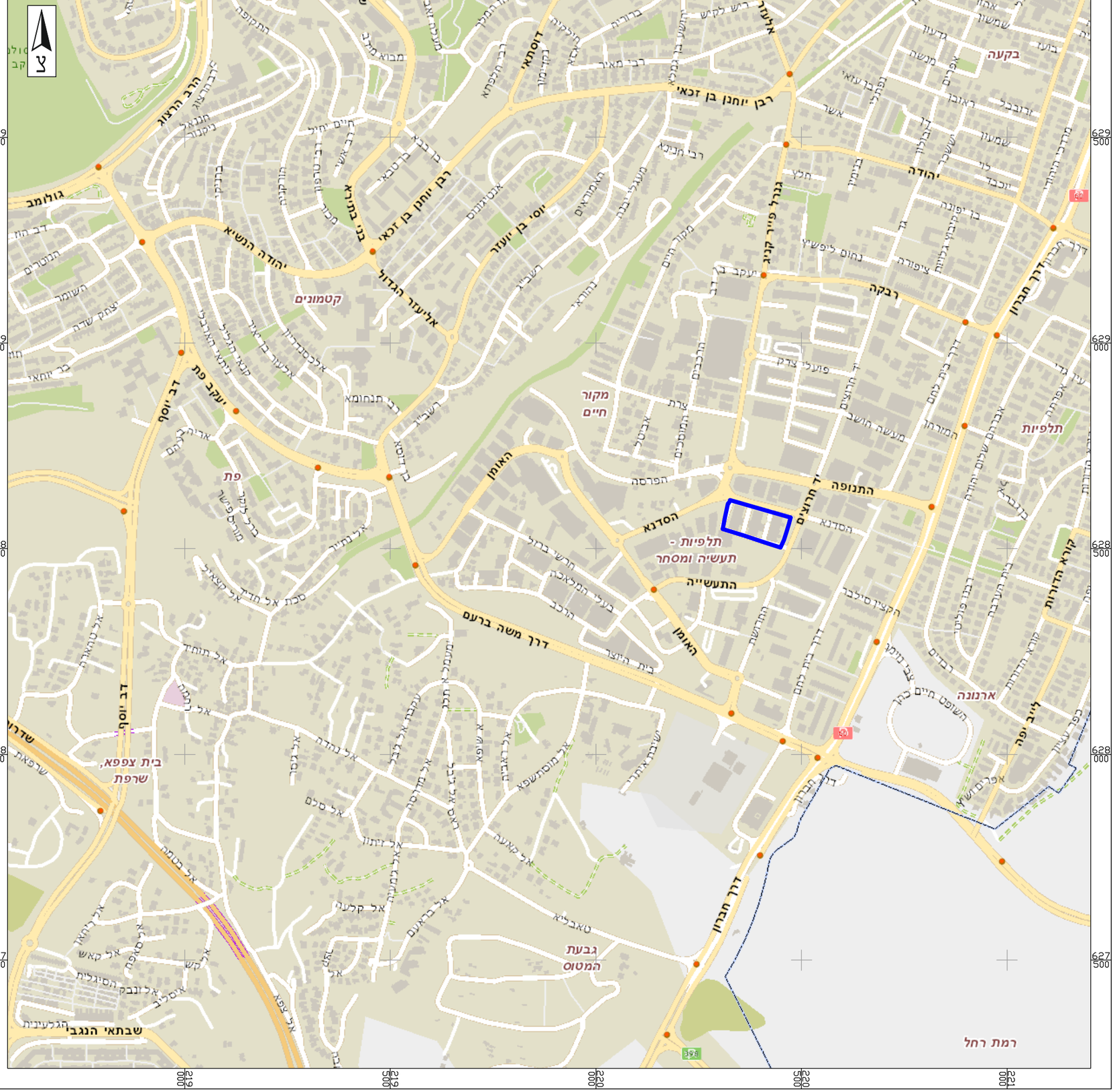

לשם שפר
איכות סביבה

תכנית 1011095330 נספח סקר קרקע היסטורי נספח קרקע היסטורי 11:17:12 20/01/2026

לשם שפר
איכות סביבה

תרשים מס׳ 2
שימושי הקרקע בסביבת המתחם מוצגים על רקע תצלום אוויר
קנ"מ 1:1,000

מס"ד	מבנה	דייר נוכחי
1	בניין 1, קומת קרקע תחתונה.	דפוס וכריכייה ינץ, פועל מאז הקמת המבנה.
2		חיבה שלטים – בית מלאכה לשלטים, בסיור נצפה כי היא עוסקת בעיקר בהבלטות והדגשת לוחיות רישוי לרכב. חיבה פועל במקום מ 1993 במבנה, לפניו פעל ביחידה בית מלאכה לשיפוץ סטרטרים.
3		יחידה סגורה, לפי השילוט והשכנים - מוסך שאול אשר נסגר.
4		מוסך שבי – מוסך מכונאות רכב, לפניו– מוסך רובין / מוסך תלפיות
5		חנות חלפים לרכב "רינאור" עוסקים רק בחלפים חדשים. חנות החלפים פועלת במקום מזה 8 שנים, לפני – עיבוד שבבי.
6		יחידה סגורה, לפי השילוט והשכנים - מוסך הסטורי אשר נסגר. לפי השכנים פעל במקום מוסך ובית מלאכה לעיבוד שבבי
7		מחסן מזון למשפחות נזקקות מזה 15 שנים.
8	בניין 1, קומה עליונה.	נגרייה, מזה שנתיים במקום, לפניה פעלה במקום נגרייה נוספת
9		נגרייה, לפני הנגרייה מחסן מוצרי מזון "עלית"
10		בית מלאכה לאלומיניום
11		מחסן סטוקים (מוצרי מזון + טואלטיקה) כ- 20 שנה. לפניו – נגרייה
12		בית מלאכה לשיפוץ סטרטרים מזה כ-20 שנה, לפניו – מחסן "דלתא"
13+14		אולם תצוגה "שאולוף ובניו" מזה 15 שנים לפחות.
15	בניין 2, קומת קרקע תחתונה.	אולם תצוגה "מקור הפרזול" משנת 2000 לפחות.
16		מנסרה, ומחסן עץ "מקור הפרזול",
17		מקור הפרזול משנת 2000 במקום, לפני - מחסן "פריגת" + חנות חומרי בניין
17		מחסן וחנות מוצרי פרזול "מקור הפרזול" מקור הפרזול משנת 2000 במקום, לפני - מחסן "פריגת" + חנות חומרי בניין.
18		חנות תמרוקים
19		מוסך אופנועים, המוסך פועל במקום מ 2006, לפני – נגרייה, ולפני הנגרייה פאב
20		מוסך חשמל רכב ומיזוג אוויר מ 2013, לפניו – מוסך מכונאות – מוסך עמיד.
21		בית מלאכה למכניקה עדינה (בעיקר ציוד לנכים) מזה 3 שנים, לפניו צמיגייה "צמיגי אולימפייה"
		מחסן וחנות מצברי שנם מ 1993.
		לפניהם חנות מצברים אחרת – י.א. שיווק מצברים מ 1978.
		ככל הנראה מפתיחת המבנה במשך זמן קצר פעל במקום מוסך מכונאות.
22	בניין 2, קומה עליונה.	אולם תצוגה וחנות מוצרי קרמיקה – קרמיק דיפו. הסטורית נגרייה + תצוגת רהיטים
23		חנות עיצוב לבית – מרכז הדקורציה הסטורית נגרייה + תצוגת רהיטים
24		אידיאל – מחסן דודי שמש וציוד חימום מזה כ 20 שנה.
25		אלרם – שיווק, שרות וחלפים למוצרי חשמל– מזה כ 50 שנה במבנה
26		אלרם – שיווק. שרות וחלפים למוצרי חשמל– מזה כ 50 שנה במבנה
27		מחסן – "מרכז החלפים" (גם שייך לאלרם)
28		אלרם – שיווק, שרות וחלפים למוצרי חשמל– מזה כ 50 שנה במבנה
29	בניין 3, קומת קרקע.	מחסן – אלרם. ככל הנראה הסטורית היה חלק ממוסך.
30		בית מלאכה ללוחות חשמל "ליטווק", משנת 2000 במבנה.
31		יחידה לא ניתנת לסקירה. הסטורית ככל הנראה בית אריזה לפיצוחים.
32		מבשלת בירה מזה כ 15 שנה במבנה, לפניהם – בית דפוס.
33		מפעל פלסטיק ועיבוד שבבי כשנה וחצי במקום, הסטורית – נגריית רהיטים – שיא רהיט
34		סטוק רהיט- תצוגת ומכירת רהיטים,כשנתיים במקום,בעבר – נגריית רהיטים שיא רהיט.
35		חנות תאורה כחצי שנה במקום, הסטורית – חנות קרמיקה "איטליקה"
36		אביזרי רכב ככל הנראה לפחות משנות השמונים.
37		צמיגייה מזה כ – 15 שנה, ולפניהם- חנות חד פעמי.
38		מסעדה – פועלת מאז שהבניין הוקם
39	בניין 3, קומת קרקע עלינה (לבניין זה 6 קומות).	אולם ארועים - פועל מאז שהבניין הוקם
40		דלתות ירושלים – תצוגת דלתות - פועל מאז שהבניין הוקם
41		מאפייה + קונדיטורייה מאפה נאמן פועלת במקום מזה 11 שנה לפחות
42		מאפייה + קונדיטורייה מאפה נאמן פועלת במקום מזה 11 שנה לפחות
43		מחסן וחנות מזרנים פועל במקום מזה 11 שנה לפחות
44		מחסן וחנות מזרנים פועל במקום מזה 11 שנה לפחות
45	בניין 3, קרקע.	בית דפוס "דפוס הגליל" פועל במקום מזה 15 שנה לפחות.
46		מוסך מכונאות, ככל הנראה מאז שהוקם הבניין

שימושים שכנים

מס"ד	שימוש
47	מסחר + משרדים (תחנת משטרה מוריה)
48	אולם ארועים + מסחר
49	מסחר
50	מסחר, מסעדה ואולם ארועים
51	מסחר
52	מוסך " סיגמא מוטורס"
53	בתי מלאכה
54	אתר בבנייה (מכללה)
55	אתר בבנייה (כביש)
56	אתר בבנייה (כביש)

A – אזור אחסנת כימיקלים

B – אזור אחסנת שמנים

סקר היסטורי

היישובים הסמוכים: האתר נמצא באזור התעשייה תלפיות בירושלים.

מפעלים סמוכים: מצפון לשטח התכנית, מעבר לרח' הסדנא קיימים מס' מבני מסחר ומשרדים.

מדרום מזרח וממזרח לשטח התכנית משתרע רחוב יד חרוצים, ומעבר לו מספר בתי מלאכה ומוסכים.

מדרום לשטח התכנית קיים אתר אשר בבנייה, לפני אתר הבנייה היה בשטח זה חניון.

ממערב לשטח התכנית קיים אתר אשר בבנייה, לפני אתר הבנייה מספר מוסכים קטנים, ומבנה רישוי.

שמורות טבע : לא אותרו שמורות טבע ו/ או גנים לאומיים ברדיוס של 1 ק"מ משטח התכנית. אותר יער נטע אדם במרחק של כ- 800 מ' מדרום לשטח התכנית.

אתרי עתיקות בסביבת האתר: שטח התכנית ממוקם בתוך אתר עתיקות מוכרז 27337/0 – ירושלים, דרך חברון.

1.4 שימושי קרקע וייעודי קרקע

התב"ע הראשונה אשר אותרה לשטח התכנית היא תבע משנת 1963, אשר מגדירה את שטח התכנית לתעשייה. ברקע המדידה של התב"ע הזו ניתן לראות ששטח התכנית איננו מבונה.

תב"ע נוספת, משנת 1971 לאיחוד וחלוקת המגרשים בשטח התכנית, ברקע המדידה של תב"ע זו ניתן לראות ששטח התכנית איננו מבונה.

בתב"ע מ 1975 ניתן לראות ברקע המדידה כי שטח התכנית מבונה.

סקר היסטורי

מפות היסטוריות מהשנים 1946, 1961, 1966 מצורפות בתרשימים מס' 3א' עד 3ג'

תב"עות משנת 1961, 1963, 1969, 1971, 1975, 1980 מצורפת בתרשים מס' 5א'- 5ה'

1.5 תצ"אות וצילומים

בניתוח תצלומי אוויר היסטוריים לשטח התכנית ניתן לראות שבשנים 1956 -1967 ניתן לראות כי יש בשטח התכנית את מעברת תלפיות.

בתצלום האוויר משנת 1968 ניתן לראות כי מעברת תלפיות נטושה / הרוסה, וניתן לראות את התחלת אזור התעשייה. ניתן לראות את דרך חברון ודרך בית לחם. רח' פייר קנינג טרם נסלל.

בתצלום האוויר משנת 2005 ניתן לראות כי אזור התעשייה בנוי.

בתצלומי האוויר מהשנים 2008 עד 2019 לא אותרו שינויים מהותיים בשטח התכנית, אך נצפו מספר מבני תעשייה אשר נהרסו (ובתהליך בינוי).

תצלומי אוויר היסטוריים משטח התכנית מצורפים בתרשים מס' 4

סקר היסטורי

1.6 מידע קרטוגרפי

שימושי קרקע סמוכים לשטח התכנית ע"ג תצלום אוויר הוצגו בתרשים מס' 2 לעיל.
מפות היסטוריות מהשנים 1947, 1961, 1966 מצורפות בתרשימים מס' 3א' עד 3ג'
תצלומי אוויר היסטוריים משטח התכנית מצורפים בתרשים מס' 4
תב"עות משנת 1961, 1963, 1969, 1971, 1975, 1980 מצורפת בתרשים מס' 5א'- 5ה'
מפת מפלסים מצורפת בתרשים מס' 6.
מפת רדיוסי מגן מצורפת בתרשים מס' 7.
מפה גיאולוגית מצורפת בתרשים מס' 8.
מפת אזורי סכנה למקורות מים כתוצאה מזיהום על ידי דלקים מצורפת בתרשים מס' 5.

1.7 מידע על הנכס

בהתאם לתכנית האב החדשה למתחם תלפיות, מטרת התכנית הינה שינוי הייעוד מתעשייה למגורים, מסחר ותעסוקה, וכן הגדלת זכויות הבנייה.
התכנית מציעה הריסת 3 מבנים קיימים ובניית 3 מבני מגורים עד 30 קומות ע"ג מסד של מסחר ותעסוקה זאת בנוסף לבניית מבנה ציבור עד לגובה של 5 קומות.
התכנית כולל הפקעות בסך 40% משטח המגרש לטובת ייעודי דרך מוצעת ומבנים ומוסדות ציבור.

שטח התכנית 13.33 דונם.

סקר היסטורי

1.8 פירוט הפעילות באתר

בשטח התכנית קיימים שלושה מבני מלאכה מסחר ומשרדים, כאשר שניים בני שתי קומות והצפוני בן 6 קומות.
במבנה הדרומי פועלים מס' מוסכים, בית דפוס, בית מלאכה לשלטים ובקומה העליונה -מחסן קרמיקה ובית מלאכה לשיפוץ סטרטרים.
במבנה המרכזי פועל מחסן מצברים "שנפ", צמיגייה, מוסך, מוסך אופנועים וחנות פרזול. בקומה העליונה – מפעל וחנות מפעל לרהיטים "שיא רהיט"
במבנה הצפוני פועל בקומת הקרקע מסחר (אביזרי רכב, קרמיקה, צמיגייה, מסעדה , אולם אירועים, מאפייה, חנות מזרנים).

פרוט בתי העסק, הקיימים וההיסטורים, לפי יחידות מופיע בסעיף 1.11 בהמשך.

דף תמונות מס' 1 מציג תמונות מהסיור במתחם.

תכנית 101-1095330 20/01/2026 11:17:12 נספח סדר קרקע היסטורי נספח קרקע היסטורי

תרשים מס׳ 3.א
מיקום התכנית על רקע מפת ירושלים 1946
קנ"מ 1:10,000

מקרא:

מיקום התכנית

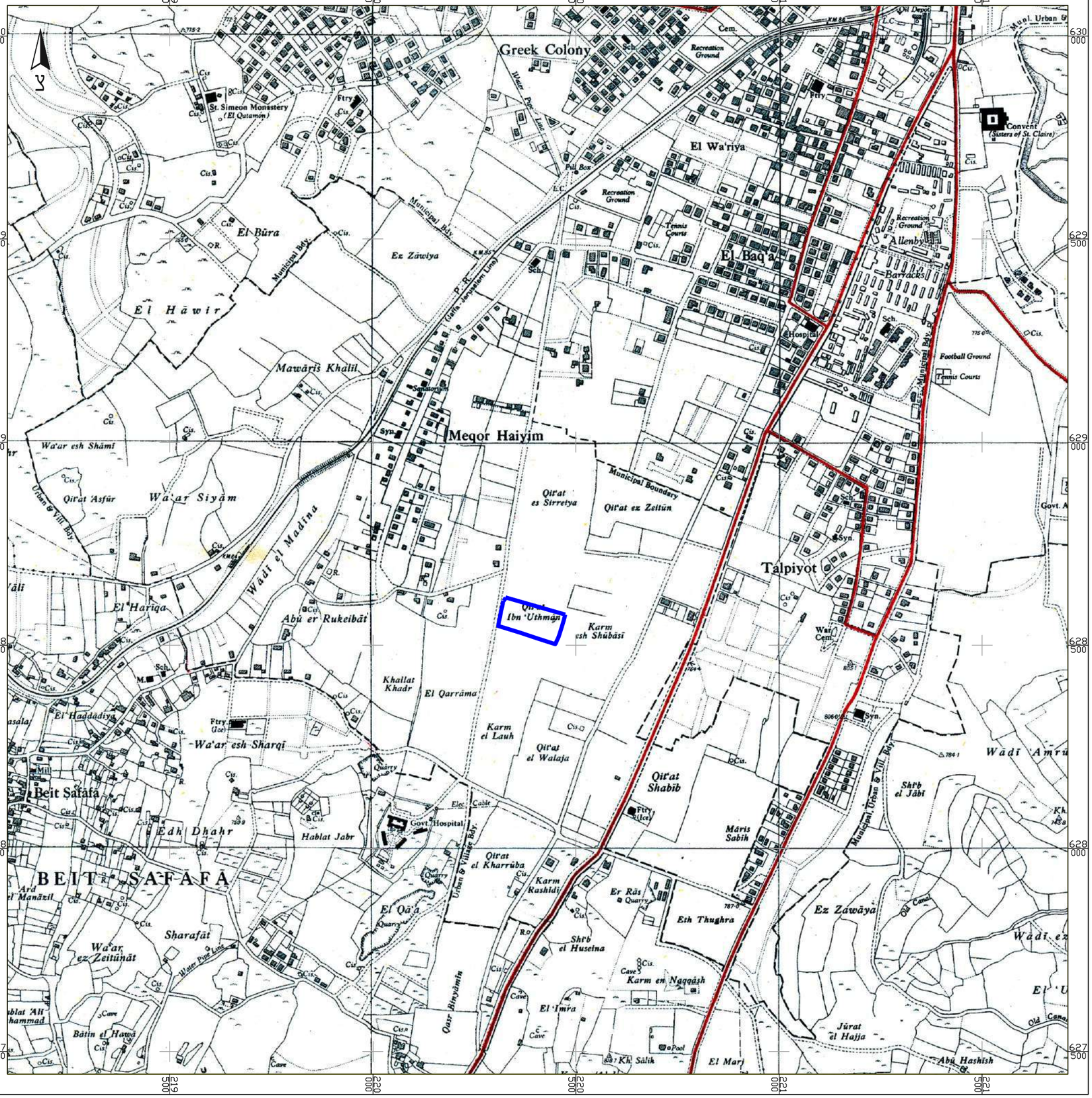
צ
Greek Colony
St. Simeon Monastery (El Qutamon)
El Bûra
Ez Zâwiya
El Hâwir
Mawâris Khalil
Meqor Haiyim
Municipal Boundary
Qit'at es Sirretya
Qit'at ez Zaitûn
El Wa'riya
El Baq'a
Allenby Barracks
Convent (Sisters of St. Claire)
Football Ground
Tennis Courts
Talpiyot
Qit'at Ibn 'Uthmân
Karm esh Shûbâsî
Wa'ar esh Shâmî
Wa'ar Siyâm
Qit'at Asfûr
El 'Hariqa
Abû er Rukeibât
Khallat Khadr
El Qarrâma
Karm el Lauh
Qit'at el Walaja
Qit'at Shabîb
Wa'ar esh Sharqî
El 'Haddâdiya
Beit Safafa
Edh Dhahr
Hablat Jabr
Govt. Hospital
BEIT SAFAFA
Sharafât
Wa'ar ez Zeitûnât
Bâtin el Hawâ
Qit'at el Kharrûba
Karm Rashîd
Er Râs
Eth Thughra
Shi'b el Huseina
Karm en Naqqâsh
El 'Imra
Jûrat el Hajja
El Mari
Abu Hashish
Ez Zawâya
Wâdî Amrû
Shi'b el Jâbi
Máris Sabîh
Municipal Urban & Vill. Bdy.
Old Canal
Water Pipe Line
P.R. (Jaffa-Jerusalem Line)
Pill Box
Recreation Ground
Tennis Courts
Cemetery
Quarry
Cave
Pool
Ruin
Mill
Sch.
Syn.
Hospital
Govt. Hospital
Elec. Cable
Urban & Vill. Bdy.
Municipal Bdy.
Municipal Boundary
Wadi el Madina
Qasr Binyâmîn
Ard el Manâzil
Wa'ar esh Sharqî
Ftry. (Uce)
Cus.
R.
Cave
Pool
Quarry
Sch.
Syn.
Hospital
Mill
Ruin
Old Canal
Water Pipe Line
Urban & Vill. Bdy.
Municipal Bdy.
Municipal Boundary

תכנית 101-1095330 נספח סדר קרקע היסטורי נספח קרקע היסטורי 20/01/2020 11:17:12

תרשים מס׳ 3.ב
מיקום התכנית ע"ג מפת ירושלים 1961
קנ"מ 1:10,000

מקרא:

מיקום התכנית

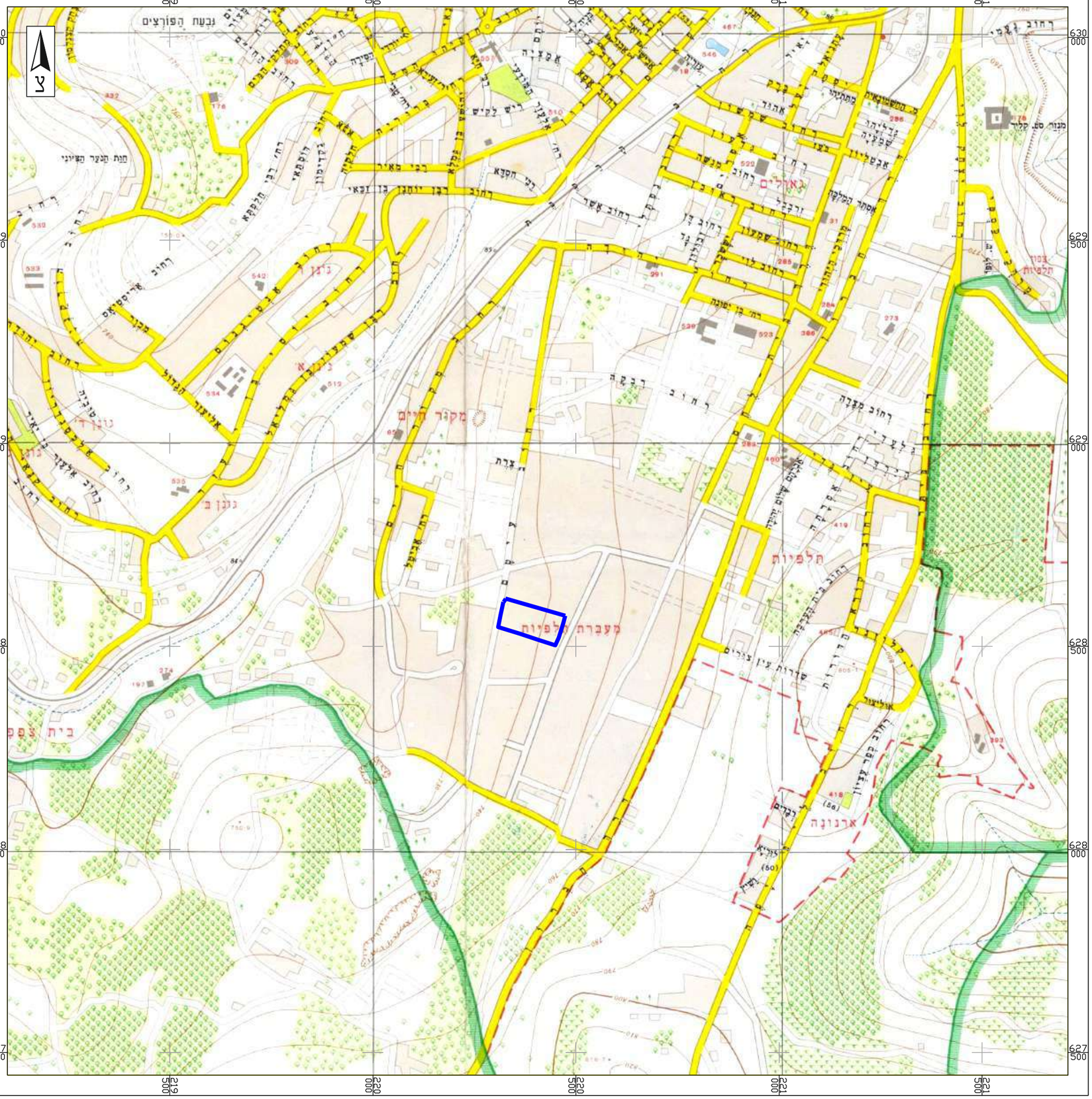

לשם שפר
איכות סביבה

תכנית 101-1095330 נספח סדר קרקע היסטורי נספח קרקע היסטורי 20/01/2026 11:17:12

תרשים מס׳ 3.ג

מיקום התכנית ע"ג מפת ירושלים 1966 קנ"מ 1:10,000

מקרא:

— מיקום התכנית

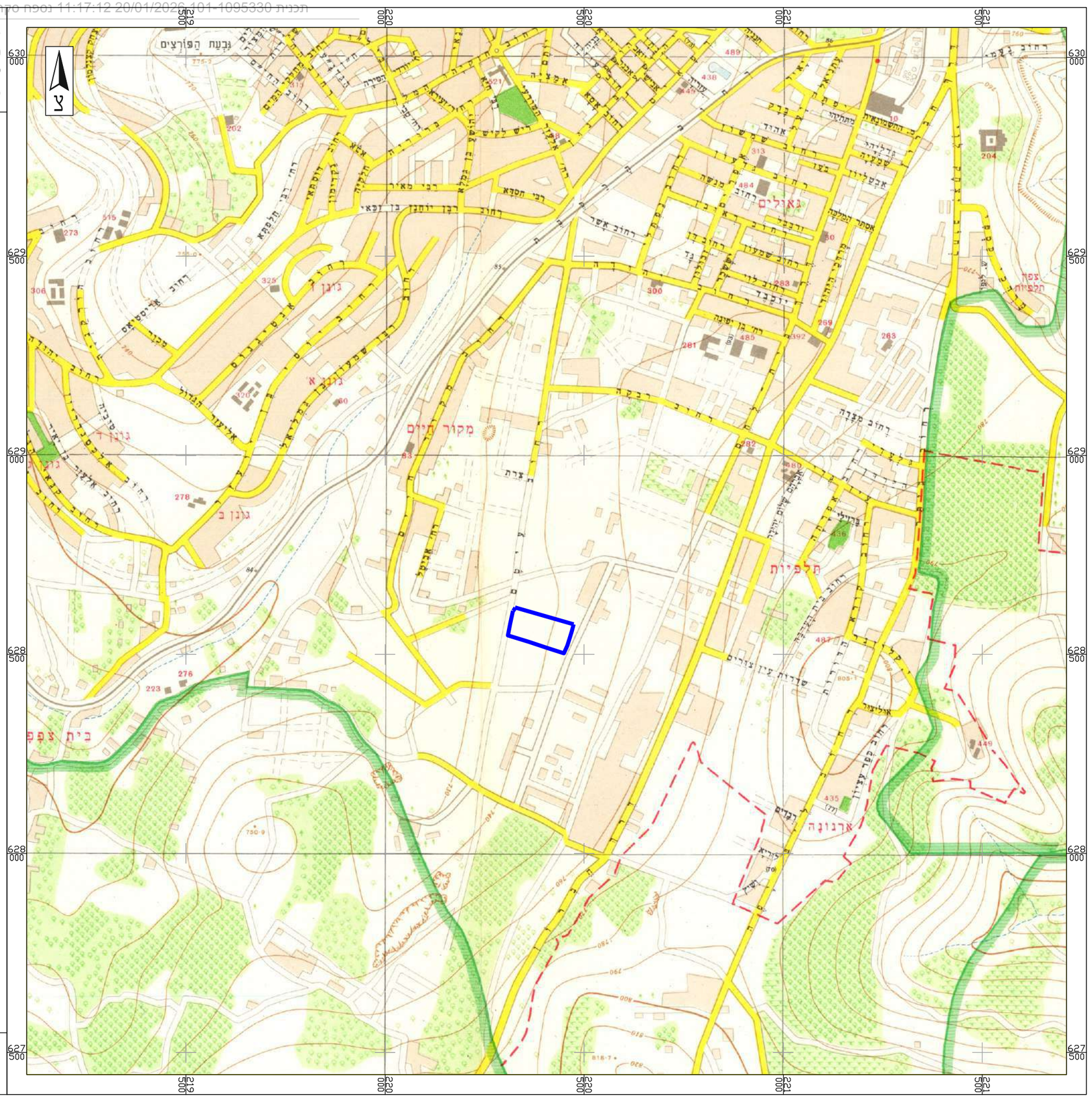

לשם שפר
איכות סביבה

תרשים מס' 4 תצ"א היסטורי
תצלומי אוויר הסטוריים עם סימון שטח התכנית
קנ"מ 1:5,000

מקרא:
- מיקום התכנית





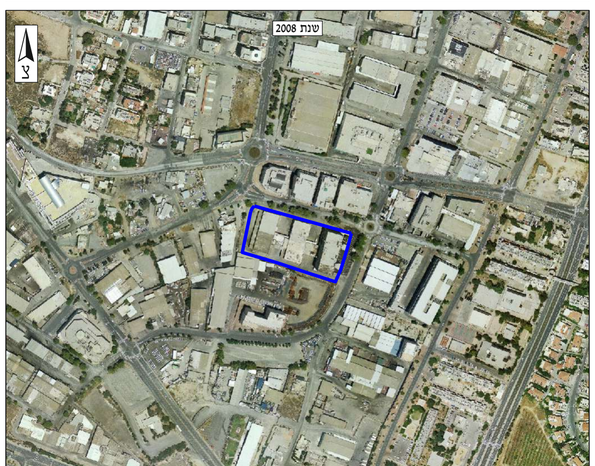

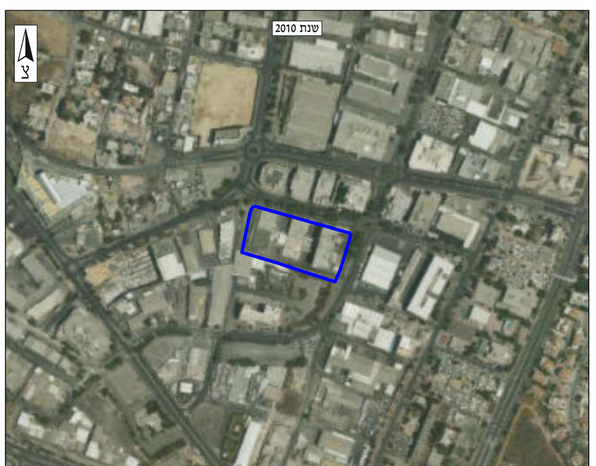

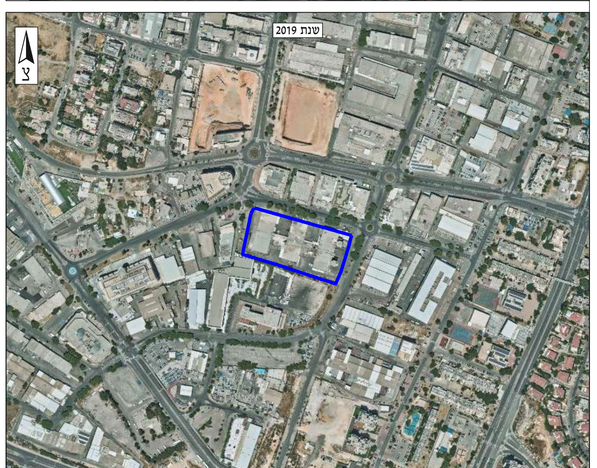

לשם שפר
איכות סביבה

תרשים מס' 5.א

מיקום התכנית ע"ג תשריט

תבע 1961

קנ"מ 1:5,000

מקרא:

גבול התכנית

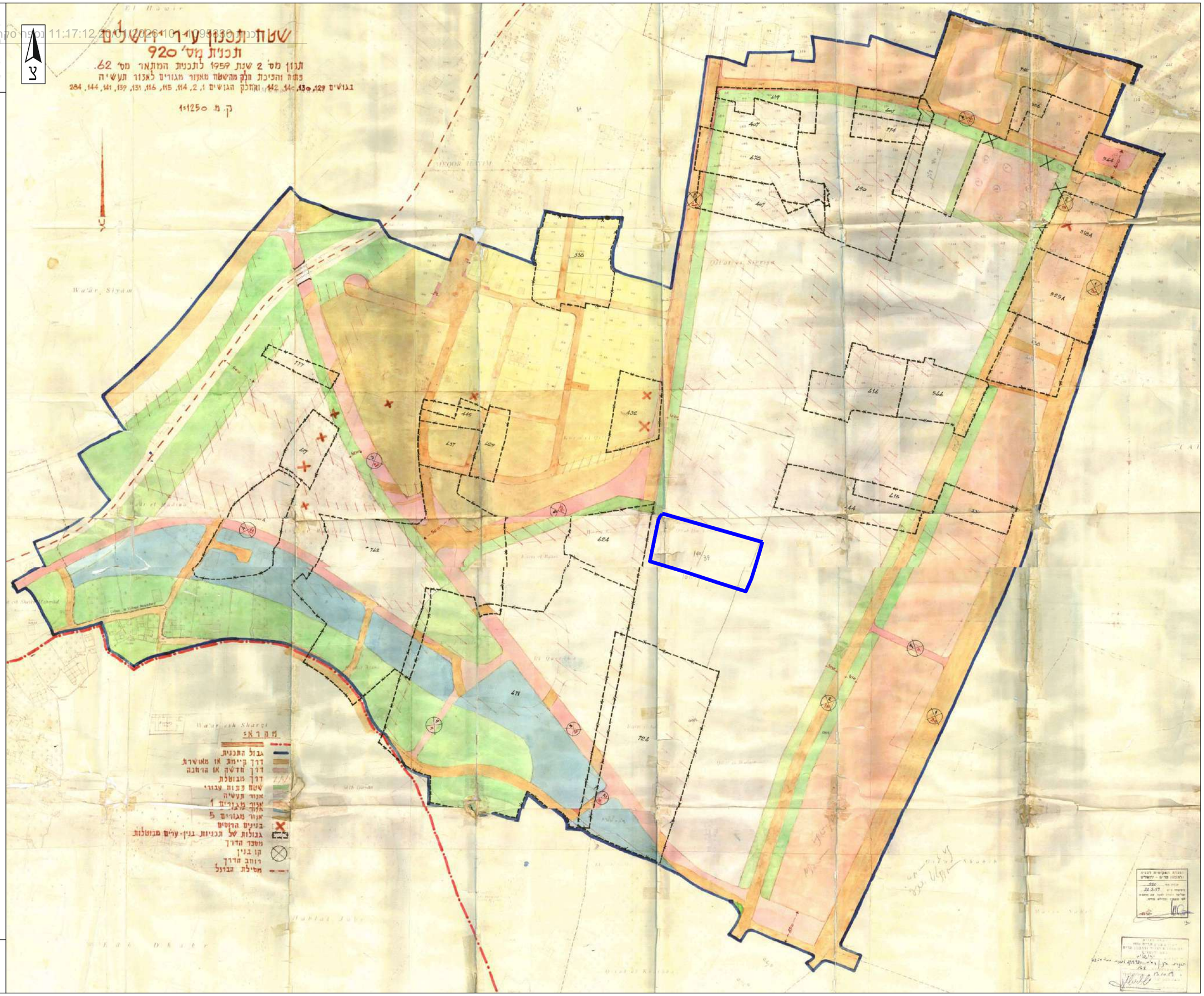

לשם שפר
איכות סביבה

תכנית 101-1095330 20/01/2026 11:17:12 נספח סקר קרקע היסטורי נספח קרקע היסטורי

תרשים מס' 2.5.ב
מיקום התכנית על רקע תשריט תבע משנת 1963
קנ"מ 1:5,000

מקרא:

מיקום התכנית

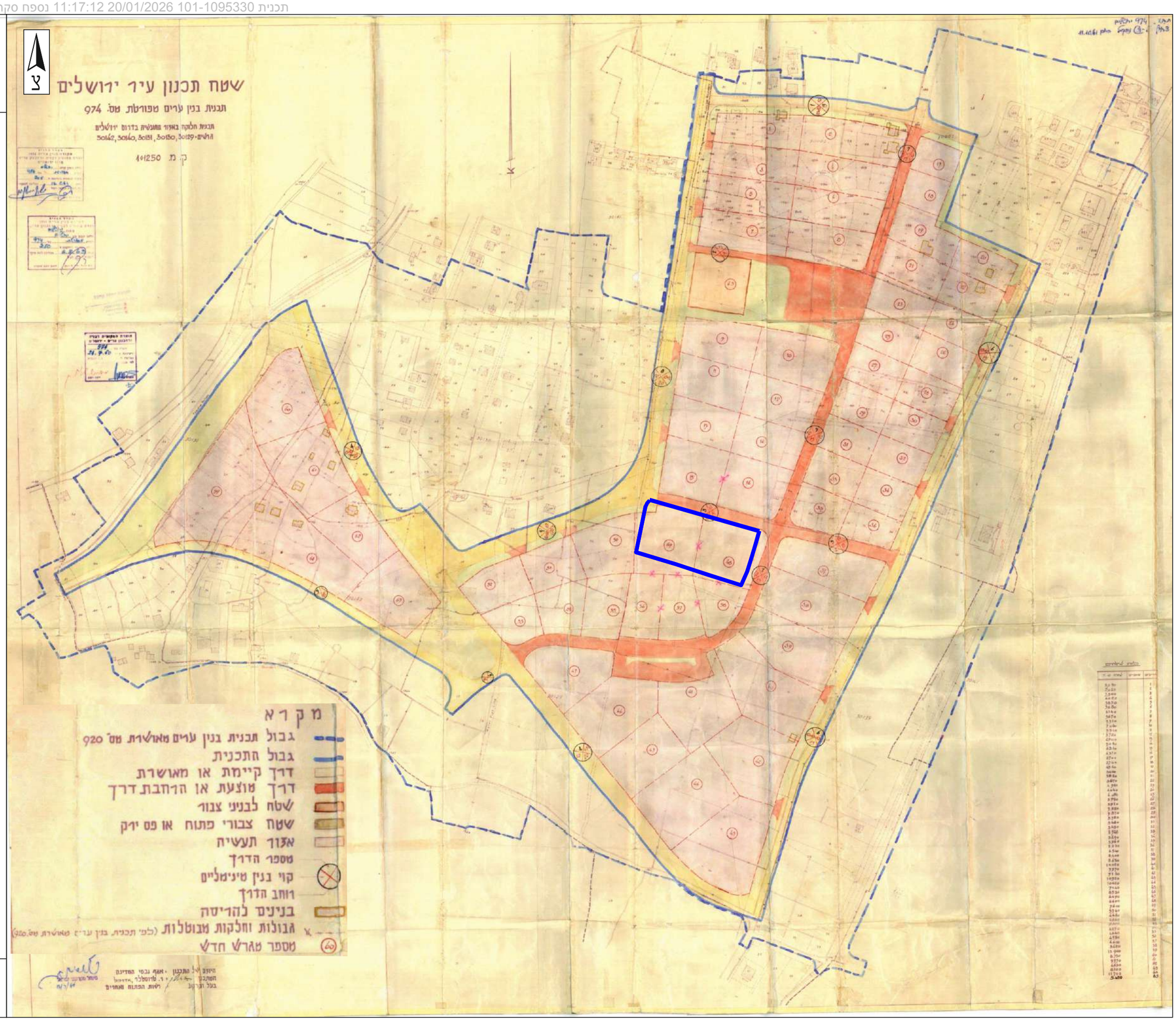

לשם שפר
איכות סביבה

תכנית 101-1095330 נספח סקר קרקע היסטורי נספח קרקע היסטורי 11:17:12 20/01/2026

תרשים מס' ג.5
תב"ע משנת 1971 עם סימון שטח התכנית
קנ"מ 1:2,500

מקרא:

מיקום התכנית

מרחב תכנון מקומי ירושלים
תשריט מצורף לתכנית תכנון עיר מפורטת מס' 1723
אחוד המגרשים 58,57,56,49,48 שבת.ת.ע. 974 חרחבת דרכים מאושרות
וביטול דרכים באזור התעשיה תלפיות

ק.מ 1:1250

טבלת שטחים

מספר המגרש	שטח המגרש במ"ר לפי ת.ת.ע 974	לתעשיה במ"ר	באחוזים	לדרך צבורית במ"ר	באחוזים
48	6600	5800	88	800	12
49	7600	7600	100	–	–
56	4950	4950	100	–	–
57	4600	4525	98,5	75	1,5
58	3620	2585	71	1035	29
סה"כ	27,370	25,460	93	1910	7

מ ק ר א

- גבול התכנית
- דרך קיימת או מאושרת
- דרך חדשה או חרחבה
- דרך לביטול
- אזור תעשיה
- שטח פתוח צבורי
- גבול מבוטל של מגרש
- מספר המגרש קיים
- מספר החלקה
- מספר מגרש חדש
- קו בנין
- גבול חדש של מגרש

תרשים הסביבה ק.מ 1:5000

חתימת בעלי הקרקע
חתימת המתכנן
תאריך

משרד הפנים
חוק התכנון והבניה תשכ"ה-1965
תכנית מקומי
מס' 1723
הוחלטה להפקיד את התכנית
ירושלים

ועדת המשנה לתכנון ובניה ירושלים
תכנית ב.מ. מפורטת מס' 1723
החלטה בישיבתה מיום 1.2.1971
לאשר את התכנית הניל לפי התנאים הכלולים בהח"מ
יושב ראש

משרד הפנים
חוק התכנון והבניה תשכ"ה-1965
תכנית מקומי
מס' 1723
הוחלטה להפקיד את התכנית
יושב ראש הועדה

לשם שפר
איכות סביבה

תכנית 101-1095330 20/01/2026 11:17:12 נספח סקר קרקע היסטורי נספח קרקע היסטורי

תרשים מס' 5.7
תב"ע משנת 1975 עם סימון שטח התכנית
קנ"מ 1:2,500

מקרא:

מיקום התכנית

מרחב תכנון מקומי ירושלים
תשריט מצורף לתכנית מס' 1723א'

שנוי מס' 1/1975 לתכנית מס' 1723 ושנוי מס' 1975/ לתכנית
המתאר המקומית לירושלים

1:1250 ק.מ

מספר המגרש	שטח המגרש במ"ר לפי תת"ע 974	לתעשיה במ"ר	באחוזים	לדרך צבורית בס"ר	באחוזים	דרך צבורית שנהפכה לאזור התעשיה בי"מ	סה"כ אזור תעשיה
48	6600	6360	90,4	240	9,5		
49	7600	7600	100	—	—		
56	4950	4950	100	—	—		
57	4600	4600	100	—	—		
58	3620	3050	92	570	8,0		
סה"כ	27,370	26560	90,5	810	9,5	495	27055

מס' המגרש לפי תכנית 1723	שטח המגרש לפי תכניות 1718-1723	מספר המגרש החדש	שטח המגרש החדש בס"ר בקירוב
		א	13550
		ב	4200
		ג	4655
		ד	4650
1	27,055		27055

מ ק ר א

- גבול התכנית
- אזור תעשיה
- בנין קיים
- מספר המגרש קיים לפי ת. 1723
- 59 מספר החלקה
- מספר מגרש חדש
- גבול חדש של מגרש

תרשים הסביבה ק.מ 1:5,000

גוש 30140

גוש 30129

הוועדה המחוזית
מחוז ירושלים
23.3.10

הוועדה המקומית לתכנון ולבניה
ירושלים
תכנית מס' 1723
הופקדה בישיבתה מיום 30.11.75
ומהליך של אישור התכנית הולך להפקדה
לפי התוראות הנהוגות בעניין
יושב ראש
מהנדס העיר

תתימת בעלי הקרקע
תתימת המתכנן
תאריך

לשם שפר
איכות סביבה

תרשים מס' 5.ה
תכנית התמצאות מתוך תב"ע
סמוכה - משנת 1980 עם
סימון שטח התכנית
קנ"מ 1:2,500

מקרא:

מיקום התכנית

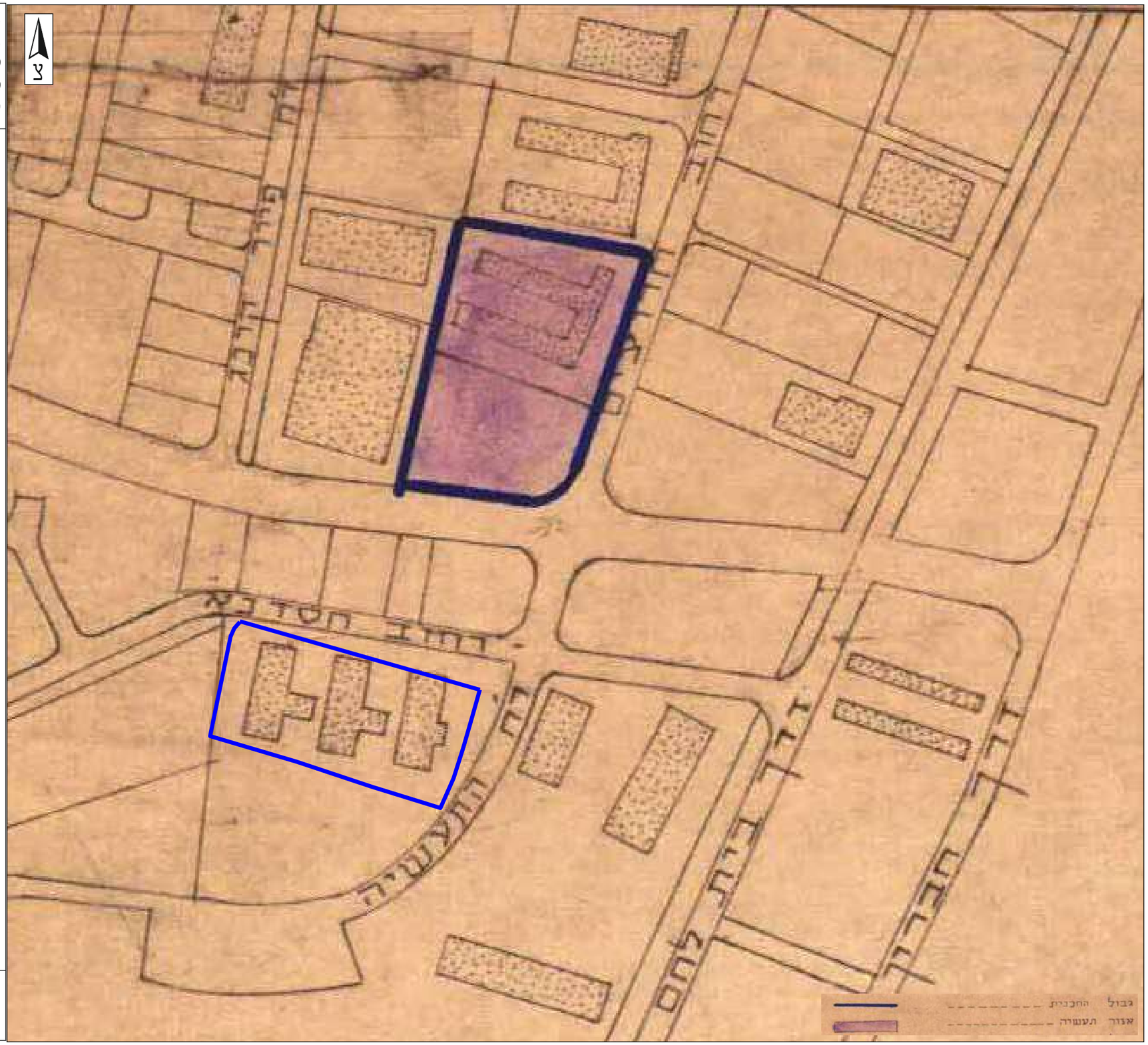

לשם שפר
איכות סביבה

לשם שפר
איכות סביבה

צ
1:250,000

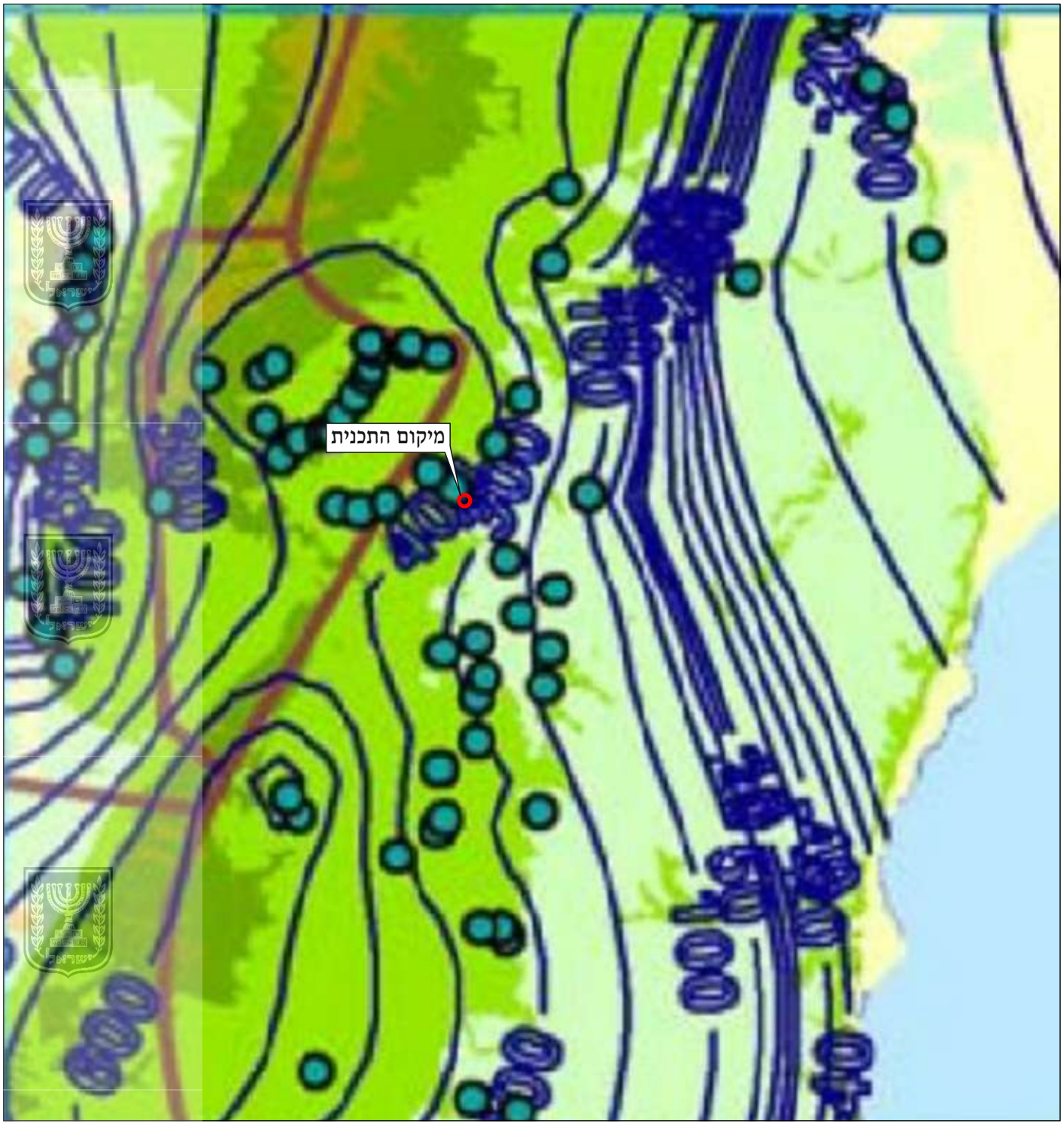

גבולות תאי ירת"ן

קווים שווי מפלס מייצגים

קידוחים עם נתוני מפלס

מפת מפלסים עם סימון אזור התכנית

תכנית 101-1095330 נספח סדר קרקע היסטורי נספח סדר קרקע היסטורי 11:17:12 20/01/2026

תרשים מס' 7
מפת אזורי מגן מקידוחים
קנ"מ 1:10,000

מקרא:

- מיקום התכנית
- אזור מגן ב'
- אזור מגן ג'

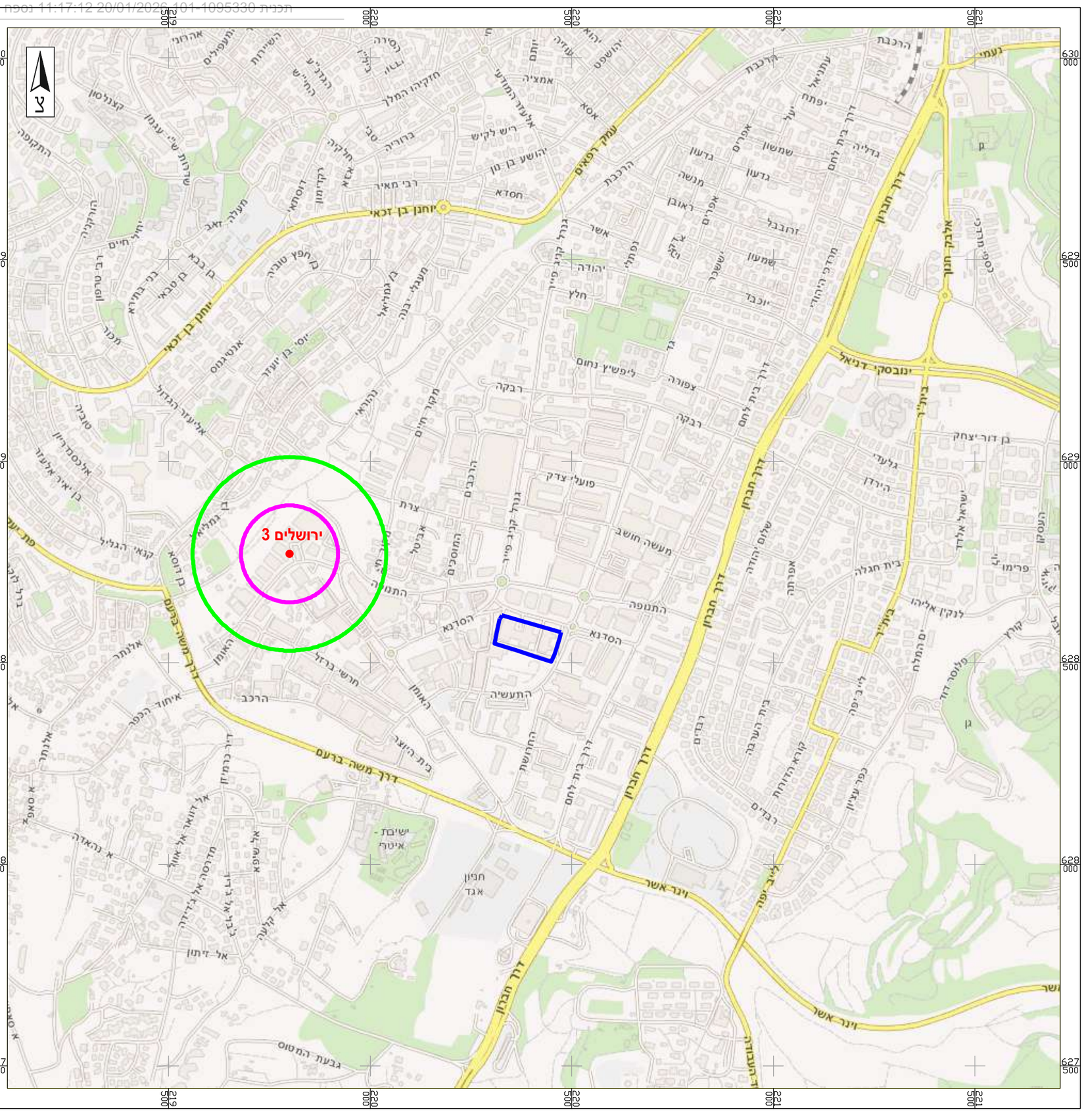

לשם שפר
איכות סביבה

תכנית 101-1095330 נספח סקר קרקע היסטורי נספח קרקע היסטורי 11:17:12 20/01/2026

תרשים מס' 8
מפה גיאולוגית עם סימון אזור התכנית
קנ"מ 1:10,000

מקרא:

מיקום התכנית

GEOLOGY **גיאולוגיה**

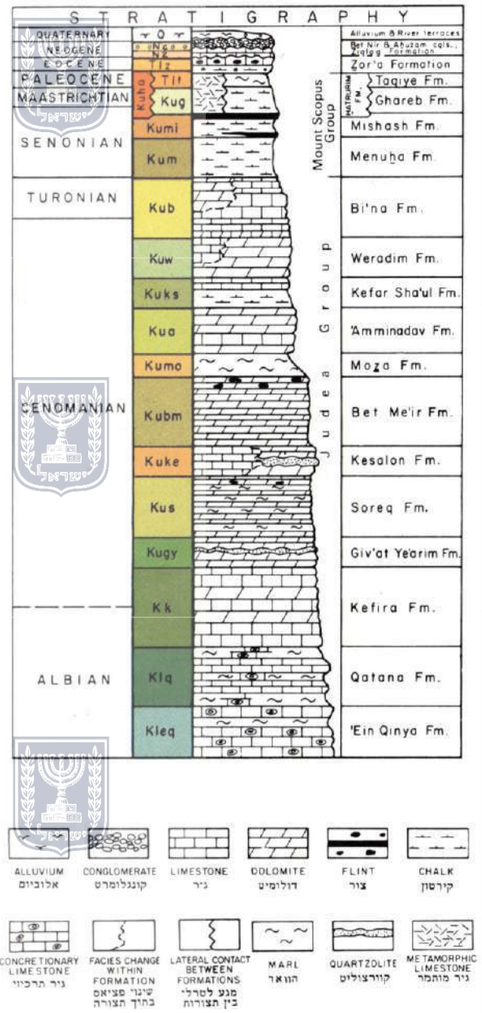

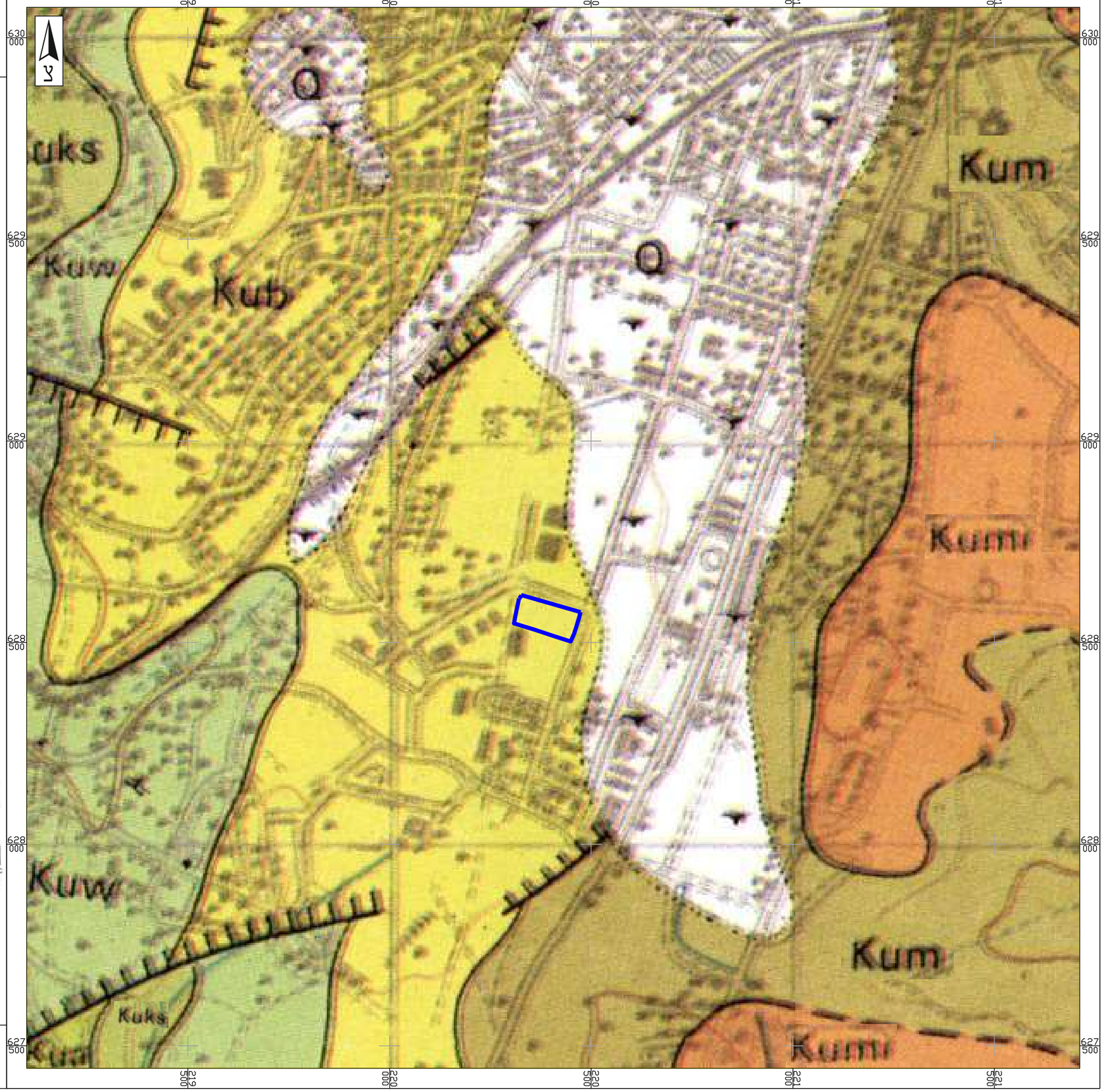

לשם שפר
איכות סביבה

תכנית 101-1095330 נספח סדר קרקע היסטורי נספח קרקע היסטורי 20/01/2026 11:17:12

תרשים מס' 9
מפת אזורי סכנה למקורות מים כתוצאה מזיהום על ידי דלק עם סימון שטח התכנית
קנ"מ 1:10,000

מקרא:

- מיקום התכנית
- מאוד רגיש - אקוויפר ראשי שבו הנזק אינו ניתן לתיקון

מפת מפתח, קנ"מ 1:3,000,000

לשם שפר
איכות סביבה

תכנית 101-1095330 20/01/2026 11:17:12 נספח סקר קרקע היסטורי נספח קרקע היסטורי

1.9 פירוט של התשתיות והתכסית באתר

התכסית באתר –הדרך, משטח החנייה, וחצר המבנה סלולים באספלט, ושטחי הבינוי - מבוטנים. לא אותרו תכניות סניטריות למבנים, אך מתיעוד וראיונות, אלו היו מחוברים לביוב העירוני ממועד הקמתם. לא אותרו תכניות למבנים הארעיים מתקופת המעברה, לא ניתן לשלול קיום בורות ספיגה מתקופה זו.

1.10 מידע הידרו-גיאולוגי

המסלע באזור התכנית שייך לחבורת יהודה ומשתייכת לתצורת בע'נה.

תצורה זו כוללת סלעי גיר ודולומיט.

התצורה מאופיינת בנוף מצוקי כאשר היא יוצרת נוף מצוקי.

מבחינה הידרולוגית, חדירות התצורה משתנה (סלעי הגיר והדולומיט בעלי חידור נמוך, אך הם סדוקים והסדקים מהווים תוואי בעל חדירות גבוהה).

חתך ליתולוגי אופייני בהרי יהודה מצורף בעמוד הבא.

מפלס מי התהום באזור התכנית הנו כ- 420 מ' מעל פני הים.

גובה פני הקרקע באזור התכנית הנו כ- 740 מ' מעל פני הים.

עובי התווך הלא רווי באזור זה הנו כ- 320 מ'.

שטח התכנית נמצא באזור א' במפת אזורי סכנה למקורות מים כתוצאה מזיהום על ידי דלקים – אקוויפר ראשי בו הנזק אינו ניתן לתיקון.

מפת מפלסים צורפה בתרשים מס' 6.

מפת רדיוסי מגן צורפה בתרשים מס' 7.

מפת גיאולוגית צורפה בתרשים מס' 8.

מפת אזורי סכנה למקורות מים כתוצאה מזיהום על ידי דלקים עם סימון שטח התכנית מצורפת בתרשים 9 לעיל.

להלן חתך גיאולוגי באזור הרי יהודה:

סקר היסטורי

תכנית 101-1095330 20/01/2026 11:17:12 נספח סקר קרקע היסטורי נספח קרקע היסטורי

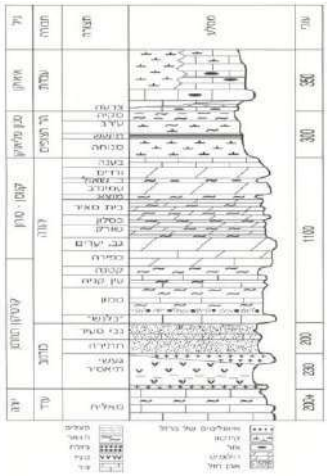

1.11 מידע על היסטוריה של זיהומים ומיפוי המידע באתר וסביבתו

להלן היסטוריה של שטחי התכנית השונים (ככל שאותר מהעירייה, ראיון עם מר אמיר רג'ואן ויחזקאל רג'ואן, ניתוח תיק תיעוד אשר הוכן למעברת תלפיות, מפות ותצלומי אוויר היסטוריים, ומקורות שונים במרשתת).

שטח האתר הנסקר היה שייך לשטחים פתוחים בין תלפיות ושכונת מקור חיים. בתחילת שנות החמישים נבנתה בשטח התכנית וסביבתה "מעברת תלפיות" אשר הורכבה מצריפונים.

המעברה פונתה במהלך שנות השישים. בתצלומי האוויר מהשנים 1958 ו- 1967 אשר צורפו בתרשים מס' 4, ניתן לראות את הצריפונים אשר בשטח התכנית וסביבתה. כאשר בתצלום האוויר מ 1968 ניתן לראות שהמעברה פורקה ופונתה.

להלן תצלומ

חתך גיאולוגי עמודי באזור הרי יהודה, מתוך גבירצמן, 2002

תכנית 101-1095330 נספח סקר קרקע היסטורי נספח סקר קרקע היסטורי 11:17:12 20/01/2026

בשנת 1963 הופקדה תכנית 974 אשר מתווה את אזור התעשייה, והדרכים.
בתשריטי התב"ע ניתן לראות ששטח התכנית אינו מבונה (צריפוני המגורים נהרסו).

בשנת 1971 הופקדה תכנית 1723 לאיחוד וחלוקה מחדש של המגרשים של התכנית וסביבתה.
בתשריטי התב"ע ניתן לראות ששטח התכנית אינו מבונה (צריפוני המגורים נהרסו ועדיין אין בינוי חדש).

בשנת 1970 הוקמה חברת "אמינפא". חברה אמריקאית לפיתוח שטחי תעשיה בע"מ. הקרקע נרכשה, והוגשה בקשה לשלושה מבני מלאכה ב 1971.

להלן קטע ממכתב למהנדס העיר על רכישת הקרקע, ופרוט בעלי המניות בחברת אמינפא (בעיקר משפחת רג'ואן):

יצחק אברמזון עורך דין, נוטריון
ISAAC ABRAMSON ADVOCATE, NOTARY

JERUSALEM, 17, SHAMAI STR. רחוב שמאי 17, ירושלים

JERUSALEM
P.O.B. 250 - TEL. 20821

ירושלים 20 מאי 1971
ת.ד. 250 - טלפון 20821

לכבוד
מהנדס העיר
עיריית ירושלים
ירושלים.

א. נ.

בהתאם לבקשת מרשתי אמינפא חברה אמריקאית לפתוח שטחי תעשיה בע"מ הנני לאשר בזה כדלהלן.

מרשתי, החברה הנ"ל, התקשרה בחוזה הנושא את התאריך 8 פברואר 1970 עם חברת חלקה 39 בגוש 30140 (ירושלים) בע"מ והמיוצגת על ידי מנהלה מר אריה קראסו ולפיו רכשה מרשתי מהשטח הכללי הרשום בשם חברת חלקה 39 בגוש 30140 (ירושלים) בע"מ בחלקה מס' 39 בגוש 30140 שטח של 34.735 דונם.

בעלי המניות של מרשתי אמינפא חברה אמריקאית לפתוח שטחי תעשיה בע"מ הם:

האחים רג'ואן חברה קבלנית לבנין בע"מ, מרחוב הסורג 2 ירושלים.
הגב' גיאורה רג'ואן, מרחוב שלום ציון המלכה 1 ירושלים
מר מוריס רג'ואן, מרחוב הסורג 2 ירושלים
הולילנד חברה להשקעות טיפון בע"מ, מרחוב הסורג 2 ירושלים
עקשר חברה ירושלמית להשקעות וטיפון בע"מ, מרחוב הסורג 2 ירושלים.

חברת אמינפא חברה אמריקאית לפתוח שטחי תעשיה בע"מ הנה חברה רשומה כחוק במשרד רשם החברות בירושלים ומס' הרשום הנו חפ/55348, וכתובתה רחוב הסורג 2 ירושלים.

הרשאים לחתום בשם אמינפא חברה אמריקאית לפתוח שטחי תעשיה בע"מ הם:

ד"ר שמחה מנדלבוים ומר מוריס רג'ואן.

הנני מצרף בזה תמצית רשום (אקסטרקט) מהרשום של החברה חלקה 39 בגוש 30140 (ירושלים) בע"מ בספר 25 פלחה דג109 וכן צלום החוזה.

בכל הכבוד

יצחק אברמזון, עו"ד
ISAAC ABRAMSON, Advocate

יצחק אברמזון, עו"ד

תכנית 101-1095330 20/01/2026 11:17:12 נספח סקר קרקע היסטורי נספח קרקע היסטורי

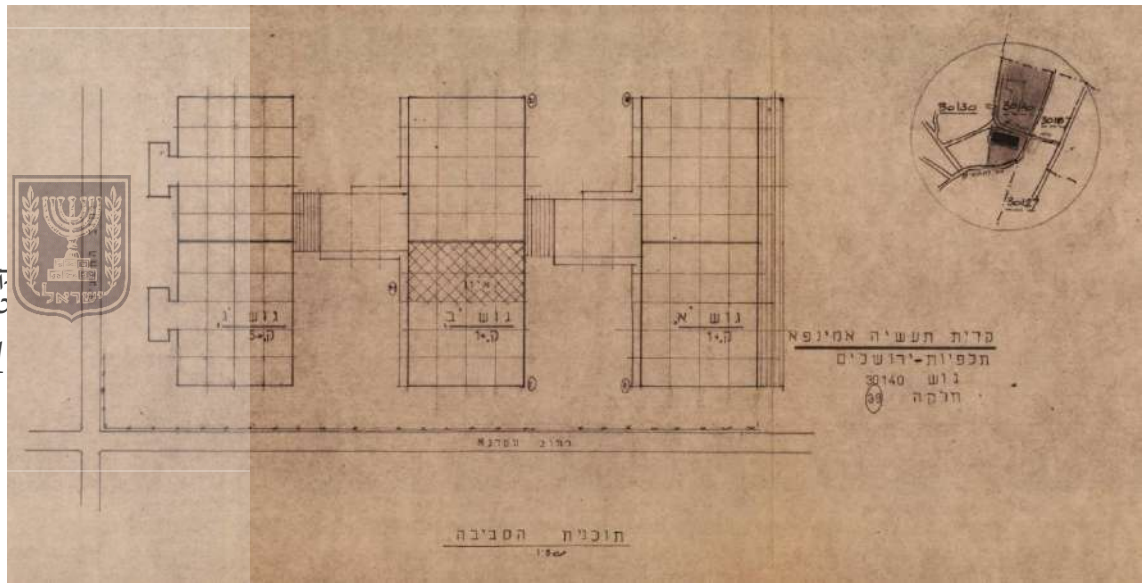

אמינפא מכרה (החכירה ל- 9,999 שנים) את היחידות במבנה לבעלי עסקים שונים, כך שיחסית תחלופת הדיירים במבנים הנה קטנה.

שטח התכנית מדורג כלפי מערב, כאשר הקומה העליונה במבנה המערבי (למשל) בנוייה מעל הקומה התחתונה, והפתח שלה לכוון מזרח, והיא מעל מפלס הקרקע בכ – 1 מ' לפחות. כך שכל היחידות עם חזית לכוון מזרח אינן במגע עם הקרקע, אלא מורמות כמטר לפחות מעל הקרקע ומעל היחידות אשר בחזית מערבית. בנוסף בד"כ בחזיתות אלו מהמידע ההיסטורי לא היו מוסכים ובתי מלאכה גדולים (עקב אי נגישות לרכב), אלא יותר אולמי תצוגה, מחסנים ובתי מלאכה קטנים.

להלן תצלום לדוגמה של בניין מס' 1 :

תכנית 101-1095330 20/01/2026 11:17:12 נספח סקר קרקע היסטורי נספח קרקע היסטורי

להלן פרוט הדיירים הנוכחיים וההיסטוריים, ככל שאותר מידע ביחידות השונות.

מספר בתרשים 2	מבנה וקומה	דייר נוכחי	תיאור היסטוריה ככל שידוע	הערות ופוטנציאל זיהום
1	בניין 1, קומת קרקע תחתונה.	דפוס וכריכייה ינץ	בראיון – בית העסק פועל במקום מאז שבנו את המבנה	לא אותר היתר רעלים, לא נצפה שפך. אותר וסומן אזור אחסנת כימיקלים, וכן אזור אחסנת שמנים. קיים חשש לזיהום בדלקים, VOC ומתכות.
2		חיבח שלטים – בית מלאכה לשלטים, בסיור נצפה כי היא עוסקת בעיקר בהבלטות והדגשת לוחיות רישוי לרכב.	חיבח מ 1993 במבנה, לפניו פעל ביחידה בית מלאכה לשיפוץ סטרטרים.	חשש קל בשמנים ומתכות.
3		יחידה סגורה, לפי השילוט והשכנים - מוסך שאול אשר נסגר.	לא אותר מידע, בית העסק סגור ולא ניתן לראיין את הבעלים	דלקים ושמנים

תכנית 101-1095330 20/01/2026 11:17:12 נספח סקר קרקע היסטורי נספח קרקע היסטורי

4		מוסך שבי – מוסך מכונאות רכב	מוסך שבי חדש במקום (כשנה) לפני – מוסך רובין / מוסך תלפיות.	דלקים ושמנים
5		חנות חלפים לרכב "רינאוי" עוסקים רק בחלפים חדשים.	חנות החלפים פועלת במקום מזה 8 שנים במקום, לפני פעל במקום בית מלאכה לעיבוד שבבי.	חשש קל לשמנים
6		יחידה סגורה, לפי השילוט והשכנים - מוסך הסטורי אשר נסגר.	הסטורית לפי השכנים פעל במקום מוסך ובית מלאכה לעיבוד שבבי.	דלקים ושמנים
7		מחסן מזון למשפחות נזקקות	פועל במקום מזה 15 שנה.	אין היסטוריה מלאה ולכן חשש קל לדלקים ושמנים
8	בניין 1, קומה עליונה.	נגרייה, מזה שנתיים במקום	לפי בעל המקום, לפניו פעלה במקום נגרייה נוספת	ללא חשש, ממוקם בקומה 1.
9		נגרייה	לפני הנגרייה מחסן מוצרי מזון "עלית"	ללא חשש, ממוקם בקומה 1.
10		בית מלאכה לאלומיניום		ללא חשש, ממוקם בקומה 1.
11		מחסן סטוקים (מוצרי מזון + טואלטיקה).	מחסן המזון פועל במקום מזה כ – 20 שנה, לפני – נגרייה.	ללא חשש, ממוקם בקומה 1.
12		בית מלאכה לשיפוץ סטרטרים	בית המלאכה פועל במקום מזה כ – 20 שנה, לפניו – מחסן "דלתא"	ללא חשש, ממוקם בקומה 1.
13+14		אולם תצוגה "שאולוף ובניו"	מזה 15 שנים לפחות.	ללא חשש, ממוקם בקומה 1.
15	בניין 2, קומת	אולם תצוגה "מקור הפרזול"	מקור הפרזול משנת 2000 במקום.	ללא חשש. תצוגה בלבד.

תכנית 101-1095330 20/01/2026 11:17:12 נספח סקר קרקע היסטורי נספח קרקע היסטורי

16	קרקע תחתונה.	מנסרה, ומחסן עץ "מקור הפרזול"	מקור הפרזול משנת 2000 במקום, לפני - מחסן "פריגת" + חנות חומרי בניין	להערכתי ללא חשש לזיהום, פעילות ניסור עץ ומחסן פרזול ועץ
17		מחסן וחנות מוצרי פרזול "מקור הפרזול"	מקור הפרזול משנת 2000 במקום, לפני - מחסן "פריגת" + חנות חומרי בניין	להערכתי ללא חשש לזיהום, פעילות ניסור עץ ומחסן פרזול ועץ
17		חנות תמרוקים		לא אותרה היסטוריית הפעילות לעסק זה ולכן לא ניתן לשלול
18		מוסך אופנועים	המוסך פועל במקום מ 2006, לפני – נגרייה, ולפני הנגרייה פאב .	שמנים ודלקים
19		מוסך חשמל רכב ומיזוג אוויר	המוסך פועל במקום מ 2013, לפני – מוסך מכונאות רכב – מוסך עמיד.	שמנים ודלקים
20		בית מלאכה למכניקה עדינה (בעיקר ציוד לנכים)	מזה 3 שנים במקום, לפני – צמיגייה צמיגי אולימפייה.	חשש קל לשמנים ודלקים
21		מחסן וחנות מצברי שנפ.	שנפ נכנסו ב 1993 למקום זה, כאשר לפניהם פעלה במקום חנות מצברים אחרת – י.א. שיווק מצברים מ 1978. ככל הנראה מפתיחת המבנה במשך זמן קצר פעל במקום מוסך מכונאות.	דלקים, מתכות כבדות וחומצות
22	בניין 2, קומה עליונה.	אולם תצוגה וחנות מוצרי קרמיקה – קרמיק דיפו	היסטורית – נגרייה + אולם תצוגה "שיא רהיט"	ללא חשש, ממוקם בקומה 1.
23		חנות עיצוב לבית – מרכז הדקורציה	היסטורית – נגרייה + אולם תצוגה "שיא רהיט"	ללא חשש, ממוקם בקומה 1.
24		אידיאל – מחסן דודי שמש וציוד חימום	הנ"ל מחסן בלבד, פועל באתר מזה כ- 20 שנה.	ללא חשש, ממוקם בקומה 1.

תכנית 101-1095330 20/01/2026 11:17:12 נספח סקר קרקע היסטורי נספח קרקע היסטורי

25		אלרם – שיווק, שרות וחלפים למוצרי חשמל	לדברי ההנהלה – מזה כ 50 שנה במבנה.	ללא חשש, ממוקם בקומה 1.
26		אלרם – שיווק, שרות וחלפים למוצרי חשמל	היסטורית, גם חלפים למוצרי חשמל "מרכז החלפים"	ללא חשש, ממוקם בקומה 1.
27		מחסן – "מרכז החלפים" (גם שייך לאלרם)	היסטורית, גם חלפים למוצרי חשמל "מרכז החלפים"	ללא חשש, ממוקם בקומה 1.
28		אלרם – שיווק, שרות וחלפים למוצרי חשמל	לדברי ההנהלה – מזה כ 50 שנה במבנה.	ללא חשש, ממוקם בקומה 1.
29	בניין 3, קומת קרקע.	מחסן – אלרם	ככל הנראה היסטורית היה חלק מהמוסך.	דלקים ושמנים
30		בית מלאכה ללוחות חשמל "ליטווק"	משנת 2000 במבנה.	ככל הנראה ללא חשש אך אין מידע היסטורי מלא
31		יחידה לא ניתנת לסקירה	היסטורית ככל הנראה בית אריזה לפיצוחים.	ככל הנראה ללא חשש אך אין מידע היסטורי מלא
32		מבשלת בירה	מזה כ 15 שנה במבנה, לפניהם – בית דפוס	חשש קל ל VOC ומתכות כבדות.
33		מפעל פלסטיק ועיבוד שבבי	כשנה וחצי במקום, היסטורית – נגריית רהיטים – שיא רהיט	חשש קל ל VOC ומתכות כבדות.
34		סטוק רהיט- תצוגה ומכירת רהיטים	כשנתיים במקום, היסטורית – נגריית רהיטים – שיא רהיט	חשש קל ל VOC ומתכות כבדות.
35		חנות תאורה	כחצי שנה במקום, היסטורית – חנות קרמיקה "איטליקה"	ככל הנראה ללא חשש אך אין מידע היסטורי מלא

סקר היסטורי

תכנית 101-1095330 20/01/2026 11:17:12 נספח סקר קרקע היסטורי נספח קרקע היסטורי

36		אביזרי רכב	בראיון עם הבעלים טען שהם במקום משנות התשעים, ולפניו- גם אביזרי רכב.	ללא חשש
37		צמיגייה	בראיון עם הבעלים טען שהם במקום מזה כ – 15 שנה, ולפניהם- חנות חד פעמי.	ללא חשש
38		מסעדה	פועלת מאז שהבניין הוקם	ללא חשש
39	בניין 3, קומת קרקע עליונה (לבניין זה 6 קומות).	אולם אירועים	תיעוד לרישיון לאולם משנות השבעים.	ללא חשש, פועל מהקמת המבנה, וממוקם בקומה 1.
40		דלתות ירושלים – תצוגת דלתות	פועל מאז שהבניין הוקם	ללא חשש, ממוקם בקומה 1.
41		מאפייה + קונדיטורייה מאפה נאמן	פועל במקום מזה 11 שנה לפחות.	ללא חשש, ממוקם בקומה 1.
42		מאפייה + קונדיטורייה מאפה נאמן	פועל במקום מזה 11 שנה לפחות.	ללא חשש, ממוקם בקומה 1.
43		מחסן וחנות מזרנים	פועל במקום מזה 11 שנה לפחות.	ללא חשש, ממוקם בקומה 1.
44		מחסן וחנות מזרנים	פועל במקום מזה 11 שנה לפחות.	ללא חשש, ממוקם בקומה 1.
45	בניין 3, קומת קרקע.	בית דפוס "דפוס הגליל"	פועל במקום מזה 15 שנה לפחות.	דלקים, שמנים, VOC, מתכות כבדות
46		מוסך מכונאות	במקום קיים מוסך, ככל הנראה מאז שהוקם הבניין	דלקים ושמנים

תכניות הסטוריות נבחרות מצורפות בנספח מס' 1.

סימון השימושים על גבי תצלום אוויר מצורף לעיל, בתרשים 2.

1.12 ניתוח ופרשנות הממצאים

בשטח התכנית הוקמו בשנות השבעים שלושה מבני תעשייה ומלאכה, כאשר שניים בני 2 קומות ואחד בן 6 קומות. היחידות במבנים הוחכרו לתקופה ארוכה (9,999 שנים). ולכן התחלופה במבנים היא קטנה יחסית.

המבנים בנויים עם הטופוגרפיה כך שקומת הקרקע היא החזיתות המערביות, וקומה ראשונה (או קומת קרקע עליונה) היא החזיתות המזרחיות, בחזיתות אלו הכניסה היא גבוהה ממפלס הקרקע בכמטר לפחות, ואין להם מגע עם הקרקע, כך שליחידות אשר בקומה העליונה אין פוטנציאל זיהום קרקע.

במבנה 1 אותר וסומן בית דפוס וותיק הכולל אזור אחסנת שמנים ואזור אחסנת כימיקלים, וכן מספר מוסכים קיימים והיסטורים, בבית הדפוס סומן אזור אחסנת כימיקלים ואזור אחסנת שמנים.

במבנה 2 אותר וסומן מוסך אופנועים, מוסך מכונאות היסטורי ובית עסק לממכר מצברים.

במבנה 3 אותר וסומן מוסך מכונאות ובית דפוס.

לא ידוע על תקלות / נזילות / אירועי חומ"ס היסטוריים מעבר למפורט לעיל אשר אירעו באתר.

לא ידוע על זיהום מי התהום באזור האתר.

הערכת רדיוס השפעה של מזהמים מהאתר על סביבתו:

טיב הקרקע הנוכחית באתר הנו קרקע רנדזינה אפורה.

המסלע הינו בעיקרו גיר ודולומיט – סלע בעל מוליכות הידראולית נמוכה, אך המסלע מאופיין במערכות סידוק מפותחות. המוליכות ההידרולוגית לאורך מערכות הסידוק הנה גבוהה יחסית.

ניתוח פוטנציאל זיהום מאתרים שמקורם הוא מחוץ לאתר:

שטח התכנית מוקף בדכים מצפון (רח' הסדנא) וממזרח (רח' התעשייה) אשר מהווים ציר ניקוז. מדרום לתכנית קיים אתר בבנייה, ללא פוטנציאל זיהום קרקע. ממערב לשטח התכנית קיים שטח בבנייה (פרוייקט הארכת רח' פייר קנינג). עם זאת, היסטורית, פעלו בשטח זה מספר מוסכים. שטח זה נמוך משמעותית משטח התכנית ואין חשש לזליגת מזהמי קרקע מאזור המוסכים לשטח התכנית, כך שאין כל חשש לזליגת מזהמי קרקע מסביבת שטח התכנית לשטח התכנית עצמו.

ניתוח פוטנציאל זיהום מהאתר על מקורות מים עיליים סמוכים ואקוויפרים:

נגר מהאתר יכול להגיע לנחל רפאים, אשר מתנקז לנחל שורק. אך לא ידוע על אירועי שפך, נזילות או זרימת מי נגר מזוהמים. לא ידוע על אקוויפר שעון באזור זה. הנגר המחלחל מגיע לאקוויפר ירת"ן.

פוטנציאל זיהום מהאתר על מבנים רגישים:

השימושים הסמוכים הם מלאכה, משרדים ומסחר. לא אותרו מבנים סמוכים רגישים.

תכנית 101-1095330 20/01/2026 11:17:12 נספח סקר קרקע היסטורי נספח קרקע היסטורי

תיאור המידע הטופוגרפי והתייחסות להערכת כיווני זרימת נגר עילי ותשטיפי שטח:
התכנית ממוקמת על רום שלוחה היורדת לכוון מערב, הנגר באזור התכנית, מנוקז לכוון נחל רפאים וממנו לנחל שורק.

זיהוי ומיפוי אזורים חשודים:

מהסקירה עולה כי נמצאו מספר אזורים חשודים, אשר משמשים כבתי מלאכה כיום או בעבר, ומחסן מצברים, כאשר מתוך בתי המלאכה, רק אלו בקומות התחתונות סומנו כבעלי פוטנציאל זיהום. בנוסף, בבית דפוס סומנו אזור אחסנת כימיקלים ואזור אחסנת שמנים.

בהתאם לממצאים, לא ניתן לשלול חשש לזיהום קרקע בשטח התכנית.
מוצעת בזאת תכנית דיגום קרקע.

1.13 בדיקה משלימה

כדי לוודא את ממצאי הסקר ולבחון האם קיים בפועל זיהום קרקע בשטחים אשר הייתה בהם פעילות בעלת פוטנציאל לזיהום קרקע, מומלץ לבצע קידוחים ובדיקות קרקע בשטח הנסקר, כדלהלן:

כאשר בבית דפוס מוצעות אנליזות TPH, מתכות כבדות ו VOC.
במוסך מכונאות : TPH
ובמחסן מצברים: TPH, מתכות כבדות ו- PH.

מס"ד	תיאור מיקום	עומק קידוח	עומקים לשליחה למעבדה	אנליזות מעבדה
1-6	בשטח, ובחצר בית דפוס " ינץ" עם דגש על אזור אחסנת כימיקלים ושמנים.	2	TPH - 1 מ' + המזוהמת ביותר לפי PID נייד (כברירת מחדל – 3 מ'). משמורת – כל 0.5 מ'. אנליזות VOC ומתכות כבדות – מהמזוהמת ביותר בלבד	TPH DRO+ORO + מתכות + VOC
7-8	בשטח בית מלאכה לשלטים "חיבה"	2	TPH - 1 מ' + המזוהמת ביותר לפי PID נייד (כברירת מחדל – 3 מ'). משמורת – כל 0.5 מ'. אנליזות VOC ומתכות כבדות – מהמזוהמת ביותר בלבד	TPH DRO+ORO + מתכות + VOC
9-18	מוסך קיים (מוסך שבי) ומוסכים הסטוריים – שאול + תלפיות	2	1 מ' + המזוהמת ביותר לפי PID נייד (כברירת מחדל – 3 מ'). משמורת – כל 0.5 מ'.	TPH DRO+ORO

תכנית 101-1095330 20/01/2026 11:17:12 נספח סקר קרקע היסטורי נספח קרקע היסטורי

19	עיבוד שבבי הסטורי	2	0.5 מ' + המזוהמת ביותר לפי PID נייד (כברירת מחדל – 3 מ'). משמורת – כל 0.5 מ'.	TPH DRO+ORO
20-22	מוסך הסטורי	2	1 מ' + המזוהמת ביותר לפי PID נייד (כברירת מחדל – 3 מ'). משמורת – כל 0.5 מ'.	TPH DRO+ORO
23	יחידה אשר לא אותר בה הסטוריית דיירים	2	TPH - 1 מ' + המזוהמת ביותר לפי PID נייד (כברירת מחדל – 3 מ'). משמורת – כל 0.5 מ'. אנליזות VOC ומתכות כבדות – מהמזוהמת ביותר בלבד	TPH DRO+ORO + מתכות + VOC
24-28	מחסן מצברים	2	TPH + PH - 1 מ' + המזוהמת ביותר לפי PID נייד (כברירת מחדל – 3 מ'). משמורת – כל 0.5 מ'. אנליזת מתכות כבדות – מהמזוהמת ביותר בלבד	TPH DRO+ORO + מתכות + PH
29-30	בית מלאכה למכאניקה עדינה (עיבוד שבבי+הדראוליקה). לא אותרה היסטוריית דיירים מלאה	2	1 מ' + המזוהמת ביותר לפי PID נייד (כברירת מחדל – 3 מ'). משמורת – כל 0.5 מ'.	TPH DRO+ORO
31-35	מוסך מכונאות היסטורי	2	1 מ' + המזוהמת ביותר לפי PID נייד (כברירת מחדל – 3 מ'). משמורת – כל 0.5 מ'.	TPH DRO+ORO
36-38	מוסך אופנועים	2	1 מ' + המזוהמת ביותר לפי PID נייד (כברירת מחדל – 3 מ'). משמורת – כל 0.5 מ'.	TPH DRO+ORO
39-40	בית דפוס היסטורי	2	TPH - 1 מ' + המזוהמת ביותר לפי PID נייד (כברירת מחדל – 3 מ'). משמורת – כל 0.5 מ'. אנליזות VOC ומתכות כבדות – מהמזוהמת ביותר בלבד	TPH DRO+ORO + מתכות + VOC
41-49	חשד למוסך היסטורי ומוסך קיים.	2	1 מ' + המזוהמת ביותר לפי PID נייד (כברירת מחדל – 3 מ'). משמורת – כל 0.5 מ'.	TPH DRO+ORO
50-51	בית דפוס	2	TPH - 1 מ' + המזוהמת ביותר לפי PID נייד (כברירת מחדל – 3 מ'). משמורת – כל 0.5 מ'.	TPH DRO+ORO

תכנית 101-1095330 20/01/2026 11:17:12 נספח סקר קרקע היסטורי נספח קרקע היסטורי

סקר היסטורי

			אנליזות VOC ומתכות כבדות – מהמזוהמת ביותר בלבד	+ מתכות + VOC

מיקום הקידוחים המוצעים מוצג בתרשים מס' 10 , על רקע תצלום אוויר.
יצוין כי העומק הסופי של הקידוחים יהיה כמצוין בטבלה, או במקרה של הגעה לשכבת סלע – אז שכבת הסלע.

תשלח הודעה על מועד ביצוע הדיגום כשבוע מראש למשרד להגנ"ס.
הקידוחים והדגימות יבוצעו ע"י דוגם מוסמך, ומעבדה מוסמכת לביצוע העבודה בנדון.
לדגימות המפורטות לעיל תתוספנה בקרות איכות (ספליט, דופליקט וכו') כנדרש.

סקר
היסטורי

תכנית 101-1095330 נספח סקר קרקע היסטורי 11:17:12 20/01/2026 נספח סקר קרקע היסטורי

תרשים מס' 10
תכנית דיגום – קרקע על רקע תצלום אוויר ושימושים
קנ"מ 1:1,000

לשם שפר
איכות סביבה

מס"ד	מבנה	דייר נוכחי
1	בניין 1, קומת קרקע תחתונה.	דפוס וכריכייה ינץ, פועל מאז הקמת המבנה.
2		חיבה שלטים – בית מלאכה לשלטים, בסיור נצפה כי היא עוסקת בעיקר בהבלטות והדגשת לוחיות רישוי לרכב. חיבה פועל במקום מ 1993 במבנה, לפניו פעל ביחידה בית מלאכה לשיפוץ סטרטרים.
3		יחידה סגורה, לפי השילוט והשכנים - מוסך שאול אשר נסגר.
4		מוסך שבי – מוסך מכונאות רכב, לפניו– מוסך רובין / מוסך תלפיות
5		חנות חלפים לרכב "רינאור" עוסקים רק בחלפים חדשים. חנות החלפים פועלת במקום מזה 8 שנים, לפני – עיבוד שבבי.
6		יחידה סגורה, לפי השילוט והשכנים - מוסך הסטורי אשר נסגר. לפי השכנים פעל במקום מוסך ובית מלאכה לעיבוד שבבי
7		מחסן מזון למשפחות נזקקות מזה 15 שנים.
8	בניין 1, קומה עליונה.	נגרייה, מזה שנתיים במקום, לפניה פעלה במקום נגרייה נוספת
9		נגרייה, לפני הנגרייה מחסן מוצרי מזון "עלית"
10		בית מלאכה לאלומיניום
11		מחסן סטוקים (מוצרי מזון + טואלטיקה) כ- 20 שנה. לפניו – נגרייה
12		בית מלאכה לשיפוץ סטרטרים מזה כ-20 שנה, לפניו – מחסן "דלתא"
13+14		אולם תצוגה "שאולוף ובניו" מזה 15 שנים לפחות.
15	בניין 2, קומת קרקע תחתונה.	אולם תצוגה "מקור הפרזול" משנת 2000 לפחות.
16		מנסרה, ומחסן עץ "מקור הפרזול",
17		מקור הפרזול משנת 2000 במקום, לפני - מחסן "פריגת" + חנות חומרי בניין
17		מחסן וחנות מוצרי פרזול "מקור הפרזול" מקור הפרזול משנת 2000 במקום, לפני - מחסן "פריגת" + חנות חומרי בניין.
18		חנות תמרוקים
19		מוסך אופנועים, המוסך פועל במקום מ 2006, לפני – נגרייה, ולפני הנגרייה פאב
20		מוסך חשמל רכב ומיזוג אוויר מ 2013, לפניו – מוסך מכונאות – מוסך עמיד.
21		בית מלאכה למכניקה עדינה (בעיקר ציוד לנכים) מזה 3 שנים, לפניו צמיגייה "צמיגי אולימפייה"
		מחסן וחנות מצברי שנפ מ 1993.
		לפניהם חנות מצברים אחרת – י.א. שיווק מצברים מ 1978.
		ככל הנראה מפתיחת המבנה במשך זמן קצר פעל במקום מוסך מכונאות.
22	בניין 2, קומה עליונה.	אולם תצוגה וחנות מוצרי קרמיקה – קרמיק דיפו. הסטורית נגרייה + תצוגת רהיטים
23		חנות עיצוב לבית – מרכז הדקורציה הסטורית נגרייה + תצוגת רהיטים
24		אידיאל – מחסן דודי שמש וציוד חימום מזה כ 20 שנה.
25		אלרם – שיווק, שרות וחלפים למוצרי חשמל– מזה כ 50 שנה במבנה
26		אלרם – שיווק. שרות וחלפים למוצרי חשמל– מזה כ 50 שנה במבנה
27		מחסן – "מרכז החלפים" (גם שייך לאלרם)
28		אלרם – שיווק, שרות וחלפים למוצרי חשמל– מזה כ 50 שנה במבנה
29	בניין 3, קומת קרקע.	מחסן – אלרם. ככל הנראה הסטורית היה חלק ממוסך.
30		בית מלאכה ללוחות חשמל "ליטווק", משנת 2000 במבנה.
31		יחידה לא ניתנת לסקירה. הסטורית ככל הנראה בית אריזה לפיצוחים.
32		מבשלת בירה מזה כ 15 שנה במבנה, לפניהם – בית דפוס.
33		מפעל פלסטיק ועיבוד שבבי כשנה וחצי במקום, הסטורית – נגריית רהיטים – שיא רהיט
34		סטוק רהיט- תצוגת ומכירת רהיטים,כשנתיים במקום,בעבר – נגריית רהיטים שיא רהיט.
35		חנות תאורה כחצי שנה במקום, הסטורית – חנות קרמיקה "איטליקה"
36		אביזרי רכב ככל הנראה לפחות משנות השמונים.
37		צמיגייה מזה כ – 15 שנה, ולפניהם- חנות חד פעמי.
38		מסעדה – פועלת מאז שהבניין הוקם
39	בניין 3, קומת קרקע עליונה (לבניין זה 6 קומות).	אולם ארועים - פועל מאז שהבניין הוקם
40		דלתות ירושלים – תצוגת דלתות - פועל מאז שהבניין הוקם
41		מאפייה + קונדיטורייה מאפה נאמן פועלת במקום מזה 11 שנה לפחות
42		מאפייה + קונדיטורייה מאפה נאמן פועלת במקום מזה 11 שנה לפחות
43		מחסן וחנות מזרנים פועל במקום מזה 11 שנה לפחות
44		מחסן וחנות מזרנים פועל במקום מזה 11 שנה לפחות
45	בניין 3, קרקע.	בית דפוס "דפוס הגליל" פועל במקום מזה 15 שנה לפחות.
46		מוסך מכונאות, ככל הנראה מאז שהוקם הבניין

שימושים שכנים

מס"ד	שימוש
47	מסחר + משרדים (תחנת משטרה מוריה)
48	אולם ארועים + מסחר
49	מסחר
50	מסחר, מסעדה ואולם ארועים
51	מסחר
52	מוסך " סיגמא מוטורס"
53	בתי מלאכה
54	אתר בבנייה (מכללה)
55	אתר בבנייה (כביש)
56	אתר בבנייה (כביש)

A – אזור אחסנת כימיקלים

B – אזור אחסנת שמנים

① נקודת דיגום קרקע מוצעת

1.14 פירוט מקורות מידע לסקר זה

מקורות המידע להכנת סקר זה היו:

- ביקור וסיורים בשטח המתחם ובסביבתו.
- סקר ספרות אודות מזהמים פוטנציאלים משימושי הקרקע הקיימים במתחם ומנגנוני הסעתם בקרקע.
- סקר ספרות אודות המבנה הגיאולוגי והסטרטגרפי של האזור.
- מאגר תצלומי אוויר היסטוריים במחלקה לגיאוגרפיה, האוניברסיטה העברית.
- מפות היסטוריות.
- ארכיון הנדסה עיריית ירושלים.
- מידע מרשות המים.
- ראיון עם מר אבי רלבג – אחראי התאום עם בעלי הנכסים מטעם רג'ואן וכן עם יחזקל רג'ואן, מנהל הנכס.
- מידע מהמשרד להגנ"ס.

נספח מס' 1

תכניות הסטוריות נבחרות

תכנית 101-1095330 נספח סקר קרקע היסטורי נספח קרקע היסטורי 11:17:12 20/01/2026

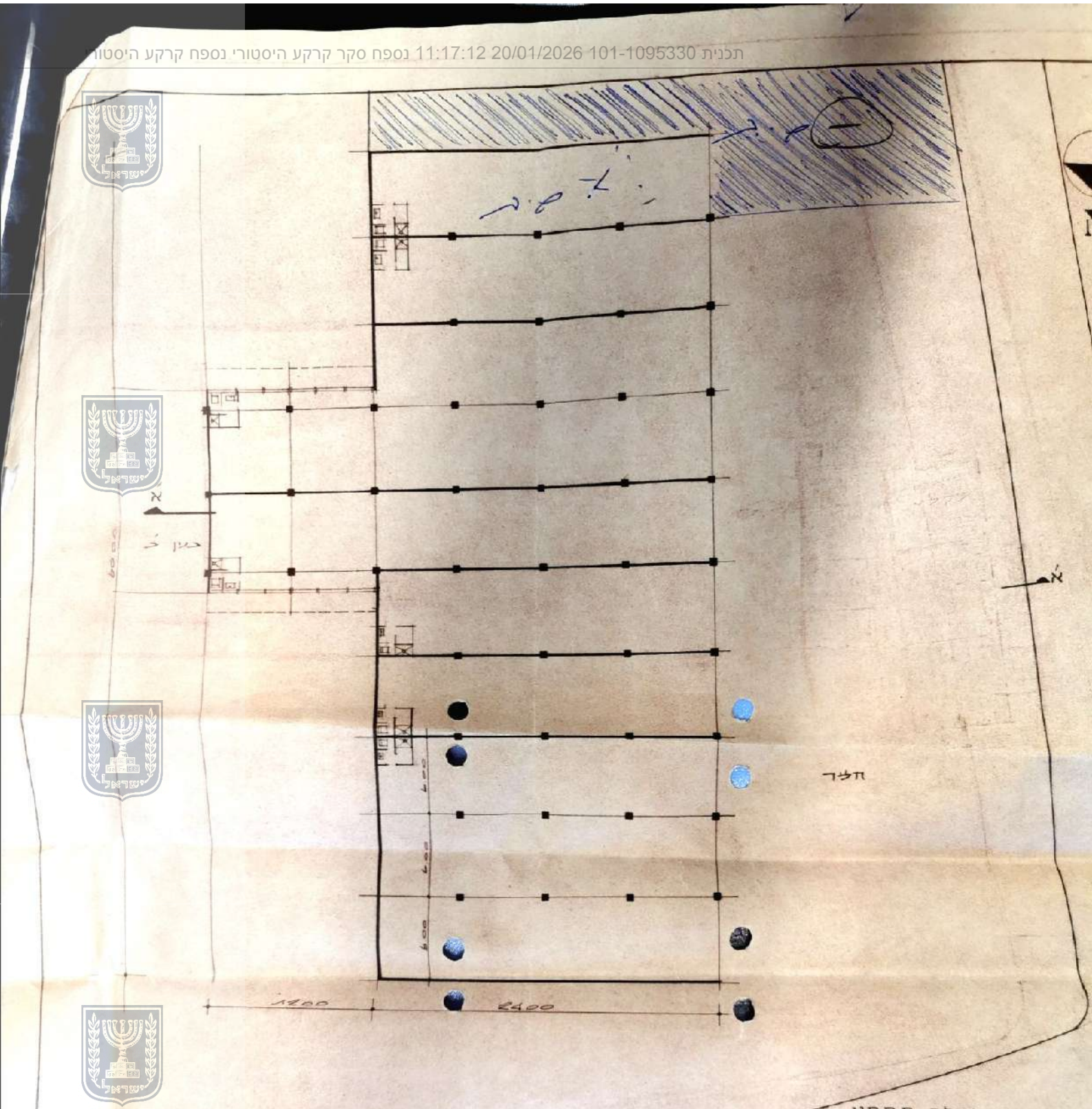

תכנית במיפלס תחתון

ק.מ 1:250

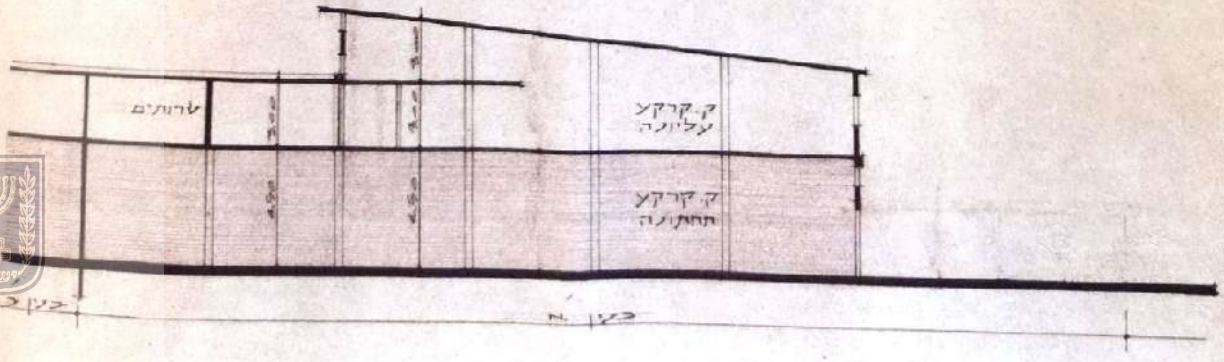

חתך א-א

תכנית 101-1095330 נספח סקר קרקע היסטורי נספח קרקע היסטורי 11:17:12 20/01/2026

הועדה המקומית לתכנון ולבניה ירושלים

30-10-2016

היתר בניה מספר № 0856

גוש 30140	חלקה 58,48,49,56,57	תיק מס' בנ/71/463

בעל ההיתר	שם אמינפא בע"מ חב' להשקעות בע"מ	מען רח' החבצלת 9, ירושלים	מס' זהות	טל'
האדריכל	שם מר בצלאל הוד	מען עין כרם 44ב', ירושלים	מס' זהות	מס' רשוי
המהנדס	שם	מען	מס' זהות	מס' רשוי

תאריך מתן ההיתר 11.11.76 היתר זה יפקע בתום שנה מיום מתן ההיתר

היתר זה אינו ניתן להעברה אלא באישור הועדה המקומית

על פי אישור הועדה המקומית לתכנון ולבניה מיום _____ מותר:

בנית קיוסק, בהתאם לתכנית א' המצורפת בזה

מקום הבנין חלפיות, ירושלים השימוש המורשה מסחרי

כל העבודות תבוצענה בהתאם לדין, לתקנות התכנון והבניה (בקשה להיתר בניה, תנאיו ואגרות) תש"ל-1970, ובהתאם לנספחים החתומים והמאושרים המצורפים להיתר זה וימולאו התנאים הכללים המפורטים מעבר לדף זה והתנאים המיוחדים הבאים:

להלן חישוב שיעור אגרת הבניה

תאור העבודה	הכמות	יח' מידה	מחיר	סה"כ
מס עבור מבנים מסחריים	25.00	מ"ר	20.00	500.00
סה"כ של המס				500.00

03.12.76

אני מאשר שהיתר זה נבדק ונמצא מתאים להחלטת הועדה	מפרעה/פקדון שולם ביום _____	מהנדס הועדה המקומית לתכנון ולבניה
	לפי קבלה מס' _____	
	יתרת אגרת בניה שולמה ביום 11.11.76	יו"ר הועדה המקומית לתכנון ולבניה ירושלים.
מנהל אגף רישוי בניה	לפי קבלה מס' 696840	

לוטה: עותק של הנספחים החתומים והמאושרים ע"י הועדה המקומית/מנהל המח' לתכנון העיר.

מאשר ע"י הועדה המקומית לתכנון ולבניה

חותמת הועדה המקומית לתכנון ולבניה ירושלים

83-328

תכנית 1095330-101/2026 11:17:12 נספח סקר קרקע היסטורי נספח סקר קרקע היסטורי

הועדה המקומית לתכנון ולבניה ירושלים

היתר בניה מספר № 0856

גוש 30140	חלקה 58,48,49,56,57	תיק מס' בנ/71/463

בעל ההיתר	שם אמינפא בע"מ חב' להשקעות בע"מ	מען רח' החבצלת 9, ירושלים	מס' זהות	טל'
האדריכל	שם מר בצלאל הוד	מען עין כרם 44ב', ירושלים	מס' זהות	מס' רשוי
המהנדס	שם	מען	מס' זהות	מס' רשוי

תאריך מתן ההיתר 11.11.76 היתר זה יפקע בתום שנה מיום מתן ההיתר

היתר זה אינו ניתן להעברה אלא באישור הועדה המקומית

על פי אישור הועדה המקומית לתכנון ולבניה מיום _____ מותר:

בניית קיוסק, בהתאם לתכנית א' המצורפת בזה

מקום הבנין תלפיות, ירושלים השימוש המורשה מסחרי

כל העבודות תבוצענה בהתאם לדין, לתקנות התכנון והבניה (בקשה להיתר בניה, תנאיו ואגרות) תש"ל-1970, ובהתאם לנספחים החתומים והמאושרים המצורפים להיתר זה וימולאו התנאים הכללים המפורטים מעבר לדף זה והתנאים המיוחדים הבאים:

להלן חישוב שיעור אגרת הבניה

תאור העבודה	הכמות	יח' מידה	מחיר	סה"כ
מס עבור מבנים מסחריים	25.00	מ"ר	20.00	500.00

סה"כ של המס 500.00

אני מאשר שהיתר זה נבדק ונמצא מתאים להחלטת הועדה

מנהל אגף רישוי בניה

מפרעה/פקדון שולם ביום _____

לפי קבלה מס' _____

יתרת אגרת בניה שולמה ביום 11.11.76

לפי קבלה מס' 696840

מהנדס הועדה המקומית לתכנון ולבניה

יו"ר הועדה המקומית לתכנון ולבניה ירושלים.

לוטה: עותק של הנספחים החתומים והמאושרים ע"י הועדה המקומית/מנהל המח' לתכנון העיר.

אושר ע"י הועדה המקומית לתכנון ולבניה

חותמת הועדה המקומית לתכנון ולבניה ירושלים

83-328

תכנית 1095330-101 נספח סקר קרקע היסטורי נספח קרקע היסטורי 11:17:12 20/01/2026

תנאים כלליים

בעל ההיתר, קבלן הבנין, מבצע העבודות, ואחראי לעמידתו וכל אחד מהם בנפרד אחראים לבצע על חשבונם ולמלא אחר התנאים הבאים:

1. העבודה תבוצע בהשגחת מהנדס רישוי ובאחריותו.
פעולות הבניה יבוצעו בהתאם להוראות למתקני הברואה תש"ל-1970.
2. יסודות הבנין וקירי הבנין יסומנו ע"י מודד מוסמך ותוגש תעודה למח' מהנדס העיר חתומה ע"י המודד המוסמך.
3. אין לעקור עץ/עצים במגרש בניה זה, אלא לאחר שאושר הדבר בכתב ע"י מנהל המחלקה לשיפור פני העיר.
4. לפני תחילת החפירה במגרש יש לפנות לחברת חשמל, למשרד הדאר, טלפונים ולמחלקת המים העירונית ולתאם העבודה איתם.
5. לפני הנחת יסודות יש לפנות למחלקת תכנון העיר לשם קבלת גובה בסיסי הגדרות והכניסות לנכס וכן לקבלת תכנית מאושרת מאת אגף הדרכים.
6. אם קיים קו ביוב או תאי ביוב בשטח הבניה המוצעת על בעל ההיתר להעתיק את קו הביוב או תא הביוב על חשבונו למקום ותאים שיאושר ע"י אגף הביוב של עיריית ירושלים. עליו לתקן על חשבונו כל נזק שיגרם לדרך כולל מדרכה או חלק ממנה או למתקן התת-קרקעי הנמצא בה כגון צנורות מים, קו ביוב, שוחות בקורת, כבלי חשמל, טלפון וכד', כתוצאה מהנחת חומר בנין או מהעברתם או בעת ביצוע העבודות לפי היתר זה.
7. יש להודיע למכון התקנים ולמחלקת תכנון העיר לפחות 3 ימים לפני יציקת כל חלק בנין הבנוי מבטון מזוין; "יש לבצע את העבודות בהתאם לחישובים הסטטיים ולסוג הבטון כפי שצויין בהצהרת המהנדס".
8. במקרה שימצאו במקום הבנין עתיקות כגון קבריס, חומות עתיקות וכד' יש להפסיק מיד את אותן העבודות היכולות לפגוע בעתיקות ולהודיע מיד על מציאותן למחלקת העתיקות.
9. יש להקים בשטח הבניה בית-שימוש זמני לשימוש הפועלים ואשר ייבנה בצורה ובמקום שתשביע את רצון מנהל המחלקה לתכנון העיר.
10. יש להקים מסביב למגרש לפני התחלת פעולת הבנין גדר מקרשים סמוכים בגובה של 2 מ' מחוזקת לשביעות רצונו של מנהל המחלקה לתכנון העיר ולהחזיקה במצב טוב במשך כל פעולות הבניה. מקום הגדר צריך להיות מסומן בתכנית הרצופה להיתר ומותר יהיה להניח חומרי בניה, כלי עבודה, פסולת או חומרים אחרים רק בתוך גבולות הגדר הנ"ל. אין בתנאים אלה כדי לגרוע מהוראות חוקי העזר לירושלים (שמירתם של רחובות) 1963.
11. יש לחבר את מערכת הביוב של הבנין עם מערכת הביוב הכללית בזמן שהדבר הוא בגדר אפשרות ובכל עת שהעיריה תדרוש זאת. היתר זה אינו כולל את ההיתר לחיבור מערכת הביוב של הבית לביוב העירוני שבעבורו יש להגיש תכנית נפרדת לאישור ולקבלת היתר ממחלקת תכנון העיר.
12. יש לסדר ניקוז אשר יפנע חדירת מי תהום או מי גשמים בקומת המרתף, למחסנים ולמקלטים.
13. יש לבצע את עבודות הפיתוח כגון: חניה כולל זיפות, בנית גדרות בגבולות המגרש, בנית מתקני אשפה עם ברז שטיפה ומחסום גלי מחובר לביוב העירוני, התקנת מתקני כביסה, גינון, בנית טרסות, נקוי שטח המגרש והסביבה לידו מכל פסולת בנין, בנית מדרכות לאורך חזית המגרש בהתאם לתכנית הכבישים המאושרת. השלמת עבודות הפיתוח תבוצע לפני סיום עבודות הבניה בבנין. לא יחובר הבנין לרשת הביוב והמים העירוניים לפני השלמת עבודות הפיתוח.
14. שפיכת אדמה או פסולת בנין וכד' תעשה אך ורק במקום שייקבע ע"י עיריית ירושלים ולאחר קבלת אישור על כך מהמחלקה לשיפור פני העיר של עיריית ירושלים.
15. יש להתקין אנטנה מרכזית לטלויזיה בהתאם לתקנות התכנון והבניה (התקנת תרנים לאנטנות טלויזיה ורדיו) תשכ"ז-1967.
16. אין לבצע עבודות האינסטלציה אלא לאחר אישור תכניות האינסטלציה ע"י מח' הספקת המים.
17. יש להתקין צנרת טלפון בבנין בהתאם לתקנות.
18. דרך הגישה הזמנית לבנית תבוצע עם תחילת הבניה ותוכשר סופית בגישה נוחה גם לשירותים עירוניים עם סיום הבניה.
19. במקומות בהם יווצרו מפלסי קרקע שונים אשר הפרש הגובה ביניהם הינו מעל 50 ס"מ, על בעל ההיתר לבנות קיר תומך עפ"י חישובים סטטיים כפי שיאושרו ע"י מחלקת תכנון העיר; יש לבנות ולהשלים הקיר התומך טרם איכלוס הבנין/התוספת ולא יאוחר מ-6 חדשים מיום חפירת השטח או תוך מועד כפי שיידרש ע"י מחלקת תכנון העיר, הכל לפי התאריך המוקדם יותר.
20. יש להתקין בבנין מעלית וגנרטור בהתאם להוראות חוק בנינים גבוהים (חובה להתקין מעלית) תשכ"ה-1965 והתקנות המתייחסות לענין.
21. יש לבנות מקלט בהתאם לחוק ההתגוננות האזרחית תשי"א-1951 ותקנותיו.
22. מתן היתר בנין זה אינו משחרר את בעליו מחובותיו כלפי דיירים או כלפי בעלי זכות אחרת לפי כל דין.
23. אין לשכן את הבנין או חלק ממנו אלא אם כן הושלמה הבניה בהתאם להיתר זה וניתנה עבורו תעודת שיכון.

לבנין יעודו [illegible] לא מאושרת

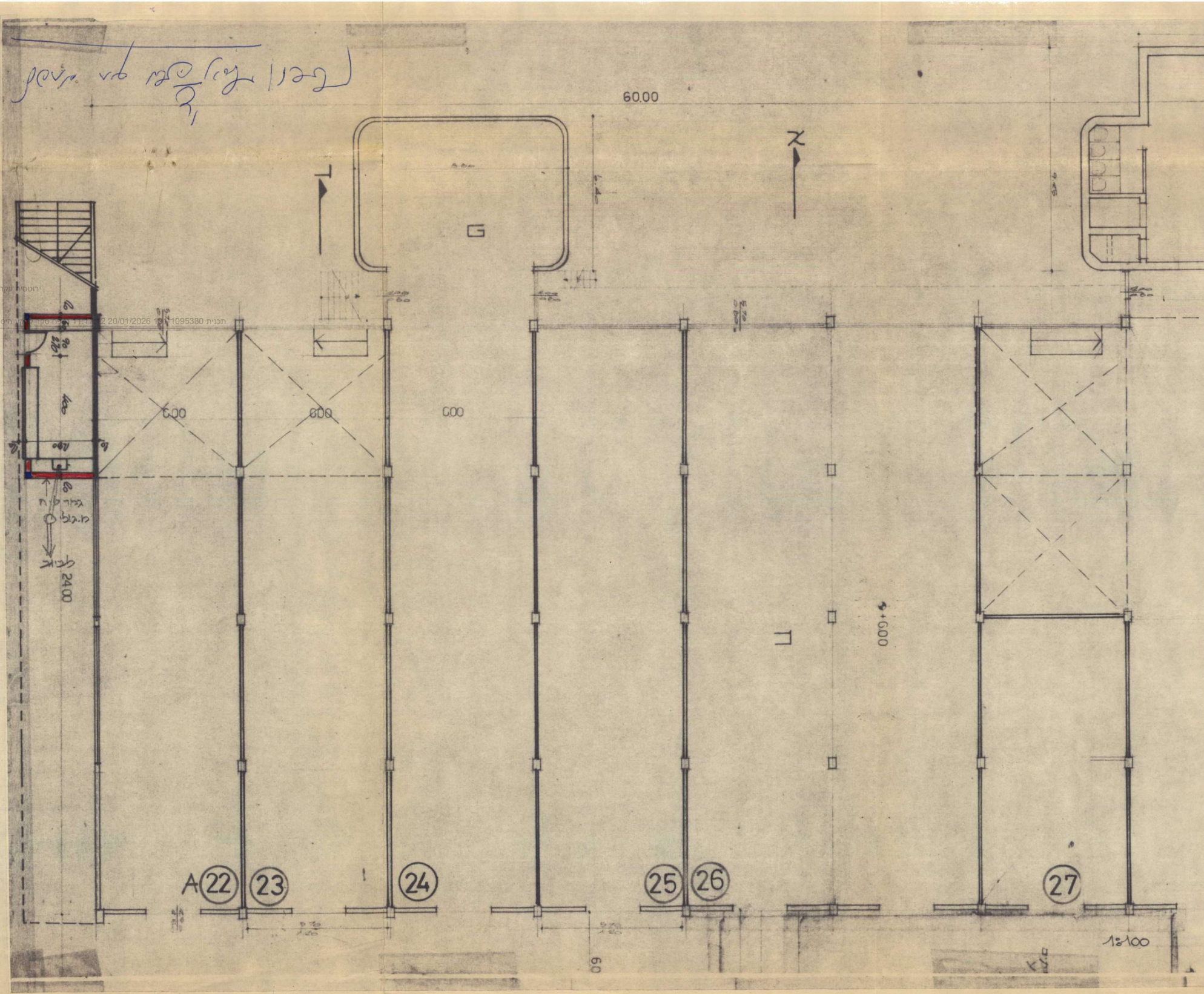
60.00
א
ד
G
6.00
6.00
6.00
גדר לבית
מ.גולי
לביוב
24.00
ב
6.00
A
22
23
24
25
26
27
1:100

ירוטסיה עקרק חפסנ ירוטסיה עקרק רקס חפסנ 12
תכנית 1095330 20/01/2026 12 נספח סקר קרקע היסטורי נספח קרקע היסטורי

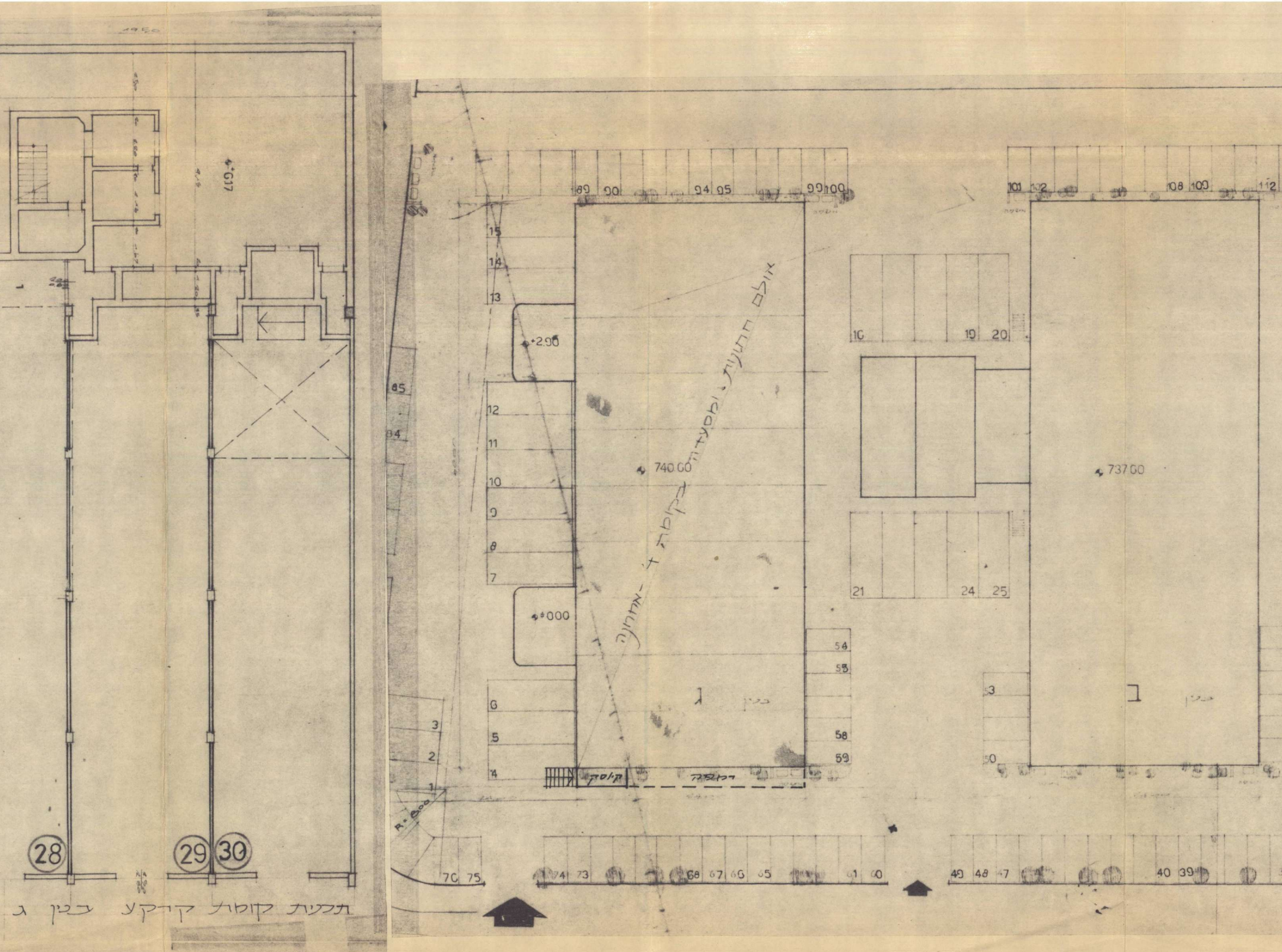
אולם חנויות ומסעדה בקומה ד - אחרונה
בנין ג
בנין ב
קיוסק
רמפה
740.00
737.00
+2.90
±0.00
617+
R=8.00
28
29
30
85
84
89 90 94 95 99 100
101 102 108 109 112
15 14 13 12 11 10 9 8 7 6 5 4
3 2 1
16 19 20
21 24 25
54 53 58 59
53 50
70 75 74 73 68 67 66 65 61 60
49 48 47 40 39

תכנית קומת קרקע בנין ג

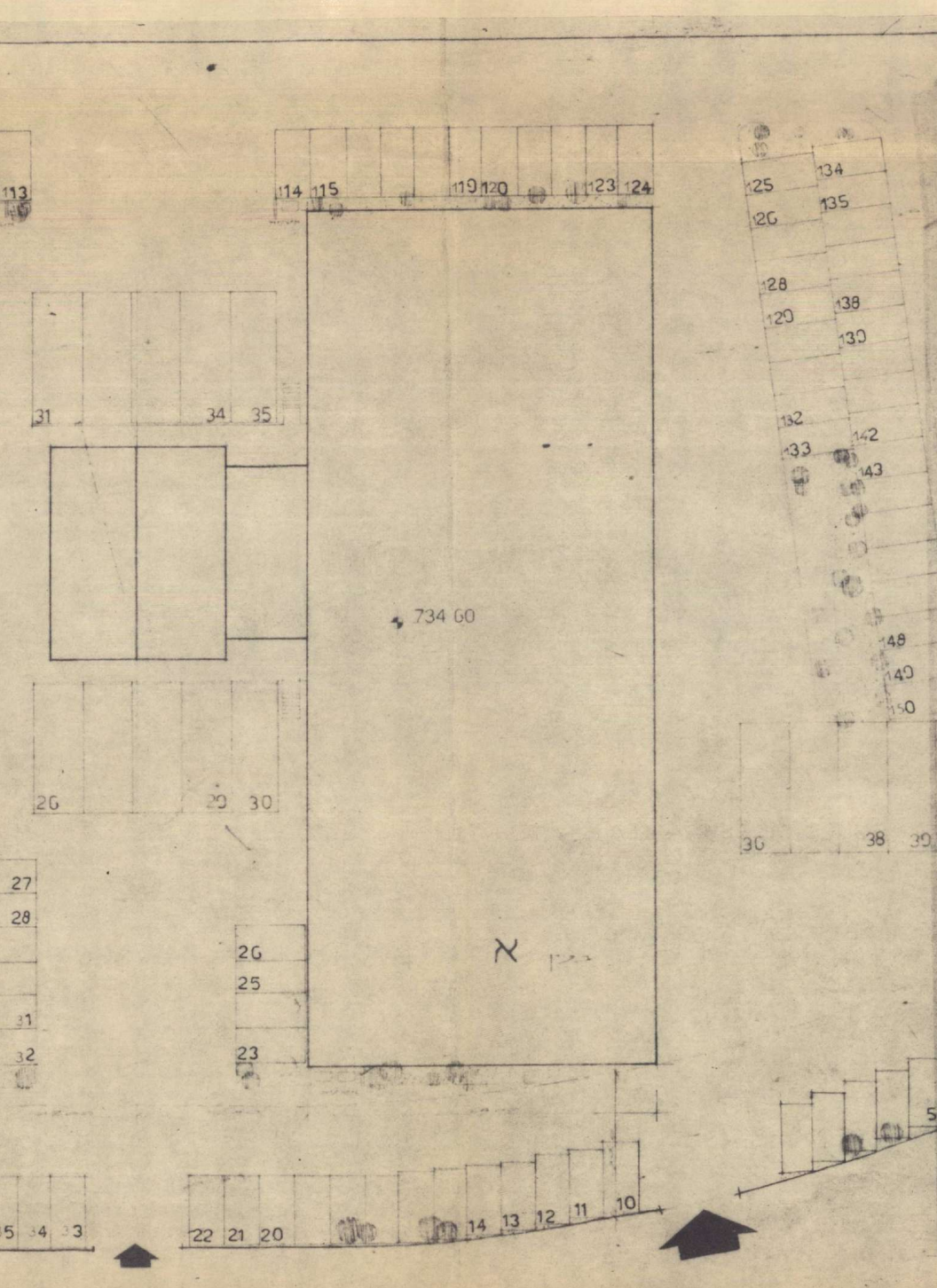
113
114 115
119 120
123 124
125 134
126 135
128 138
129 139
132 142
133 143
148
149
150
31 34 35
26 29 30
30 38 39
27
28
26
25
31
32
23
734.60
א
5
22 21 20
14 13 12 11 10
5 34 33

מקור חיים
רמת רחל
ארנונה

תרשים הסביבה קנ"מ: 1:10.000
א׳נפ׳

① [illegible]

71/463 [illegible]

חוק התכנון והבניה, תשכ״ה—1965

תקנות התכנון והבניה (בקשה להיתר, תנאיו ואגרות), תש״ל — 1970

טופס 2 (תקנה 2(א))

הוועדה המקומית לתכנון ולבניה ירושלים

מיפרט

תיק מס׳

א. תיאור הבנין

1. המקום	הרחוב	מס׳	גוש	חלקה	התכנית מיתאר מקומית או מפורטת	מגרש
תלפיות			30140	48,49 56,57,58	9-74	

השם		המען	מס׳ הטלפון
2. המבקש	״אמיפא״ חברה להשקעות בע״מ	חבצלת 9 ירושלים	
3. בעל הנכס	״		
4. עורך הבקשה	בצלאל הוד - אדריכל,	עין כרם ב 44 י-ם	
5. המהנדס האחראי לביצוע השלד			

6. אזור הבניה: ☐ מגורים ☐ מסחר ☒ תעשיה ☐ בנין ציבורי ☐ חקלאי ☐ ....

7. שטח: המגרש/החלקה: ....מ״ר. אחוז הבניה המותר: % ....

8. מטרת הבנין: ☐ מגורים ☒ הארחה ☐ עסקים ☒ תעשיה ☐ חקלאי ☐ ציבורי ☐ ....

9. מהות הבנין ותכליתו

10. תיאור העבודה המוצעת: ☒ בנין חדש ☐ תוספת לבנין קיים ☐ הריסה ☐ תיקונים ☐ שינוי בבנין ☐ ....
☐ שינוי בשימוש ממטרה: .... למטרה: ....

11. האם הבניה היא בעד: ☐ משרד ממשלתי ☐ הרשות המקומית ☐ הסוכנות היהודית

ב. היקף הבניה

קומה	קיים	מוצע	סך הכל	אחוז הבניה	שטח כולל של בניה (מ״ר)							מס׳ חדרים	
					מגורים בדירות				עסק, הארחה, וכו׳	ציבורי	שונות		
					עד 45 מ״ר	עד 65 מ״ר	עד 90 מ״ר	מעל 90 מ״ר				קיים	מוצע
1	2	3	4	5	6	7	8	9	10	11	12	13	14
מרתף													
הכניסה הקובעת לבנין													
א													
ב													
ג													
ד													
ה													
ו													
ז													
חדרי מדרגות													
בניני עזר													
סך הכל													

עירית ירושלים
מחלקת מהנדס העיר
1 .. IX. 1974

הנפח המוצע: של הבנין העיקרי ....מ״ק. של בנין עזר ....מ״ק.

ג. השימוש בבנין

1. הבניה המוצעת למגורים

דירות בנות:	שטח כל דירה מ״ר	מספר דירות מכל סוג	שטחים—מ״ר				מספר חדרים				
			כל הדירות	מזה							
				רצפות חדרי דיור בלבד, ומרפסות מקורות	רצפות חדרי שירות ופרוזדורים בלבד	רצפות של מרפסות בלתי מקורות	דיור	מטבחים	אמבטיות	בתי שימוש	אחרים
1	2	3	4	5	6	7	8	9	10	11	12
חדר אחד	ראה תשריט סכימתי של קומות הבניה בכל קומה, המציין מספר החדרים ושטח כל דירה.										
2 חדרים											
3 חדרים											
4 חדרים											
5 חדרים											
6 חדרים											
7 חדרים ויותר											
חדרים נוספים לדירות קיימות											
בניני עזר											
סך הכל											

תכנית א לבע׳ הבקשה

עירית ירושלים
תכנית מאושרת המצורפת לרשיון בנין
מס׳ 856 והמהוה חלק ממנו.
תאריך 3.12.76
מהנדס העיר

2. הבניה הקיימת והמוצעת לתעשיה ולמלאכה

פרטים	קיים				מוצע				סך הכל			הערות
	שטח	גובה	נפח	% הבניה	שטח	גובה	נפח	% הבניה	שטח	נפח	% הבניה	
1	2	3	4	5	6	7	8	9	10	11	12	13
אולמי מלאכה												
משרדים												
חדרי שירות												
סככות												
בניני עזר												
חדרי מדרגות												
סך הכל												

3. הבניה המוצעת למטרות אחרות (הארחה, עסקים ומשרדים, בניני ציבור, בניני משק חקלאי, מטרות שונות).

השימוש המיועד	שטחים—מ״ר					מספר החדרים, אולמות וכו׳			
	סך הכל מ״ר	מזה							
		חדרים	אולמות	אחסנה	חדרי שירות	חדרים	אולמות	אחסנה	חדרי שירות
1	2	3	4	5	6	7	8	9	10
בניני עזר (למעט אלה המפורטים ב־ג(4))									

4. חלקי בנין אחרים — הבניה המוצעת, שטח במ״ר.

חדרי מדרגות	כרפסות שלא נכללו לעיל	מעליות	חדרי הסקה	חדרי כביסה	מקלטים	קומת עמודים מפולשת	מחסנים	מוסכים	בניני עזר נוספים	סך הכל
1	2	3	4	5	6	7	8	9	10	11

ד. חומר הבניה

קירות חיצוניים	☐ בטון מזוין	☒ לבני בטון או בלוקים	☐ לבני סיליקט	☐ לבנים שרופות	☐ אבן טבעית
	☐ אבן מלאכותית	☐ איטונג	☐ עץ	☐ ברזל	☐ חמרים אחרים
תקרות	☒ בטון מזוין	☐ עץ	☐ חומר אחר		
גג	☒ בטון מזוין	☐ רעפים	☐ אסבסט	☐ פח	☐ חומר אחר ....

ה. גדרות

קיימות ....מ״א מוצעות ....מ״א

ו. מקרא

🟦 בטון או בטון מזוין	🟥 אבן	☐ עץ	☐ איטונג
🟩 בלוקים או לבנים מבטון	☐ סיליקט או לבנים אדומות	☐ חומר אחר	☐ להריסה

הערות: ....

הנני מאשר כי הנתונים הנ״ל נכונים

תאריך 1674 חתימת המבקש ____________ חתימת עורך הבקשה ____________

חתימת המהנדס האחראי לביצוע השלד ____________ חתימת בעל הנכס ____________

לשימוש הוועדה המקומית בלבד	מס׳ ההיתר	תאריך ההיתר	תאריך התחלת הבניה	תאריך גמר הבניה

אישורים של רשויות חוץ:

חותמת הוועדה המקומית

ד.פ. ר״ה גלופה





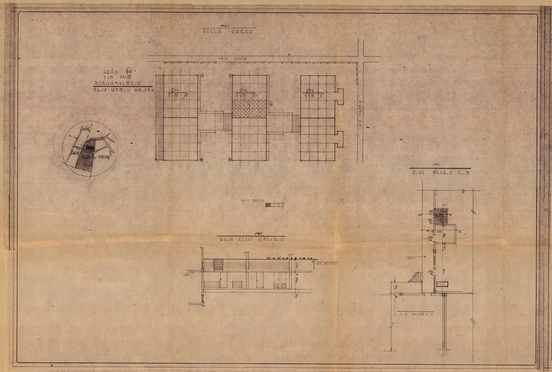

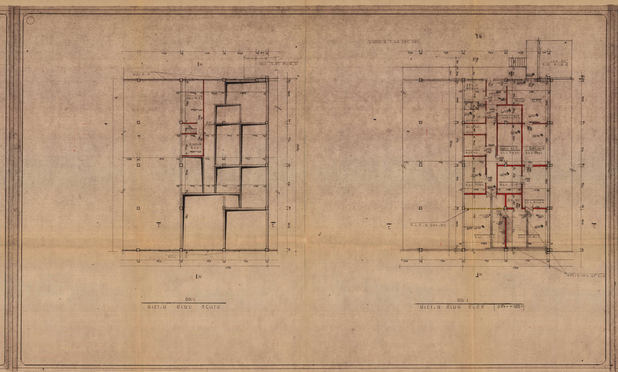

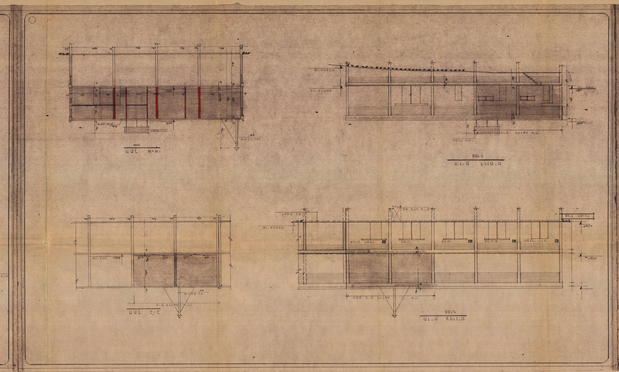

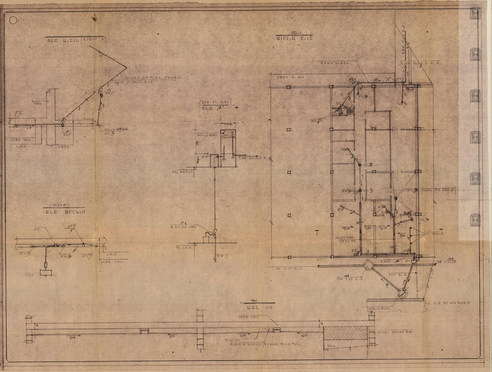

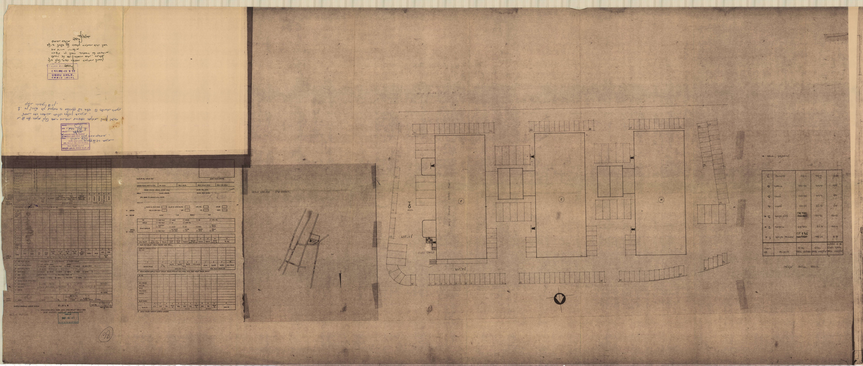

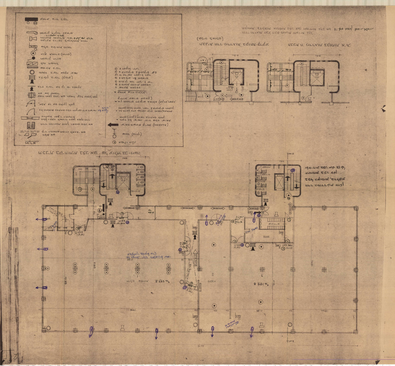

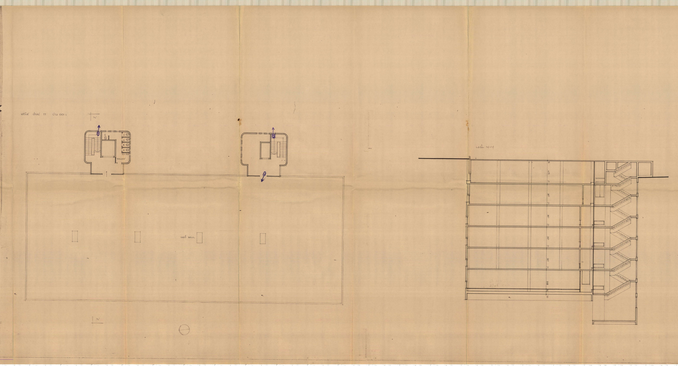

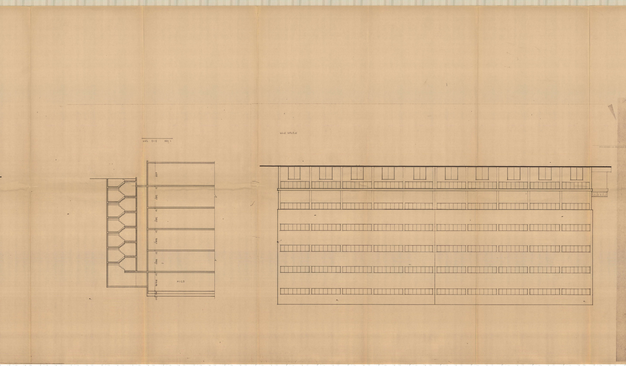

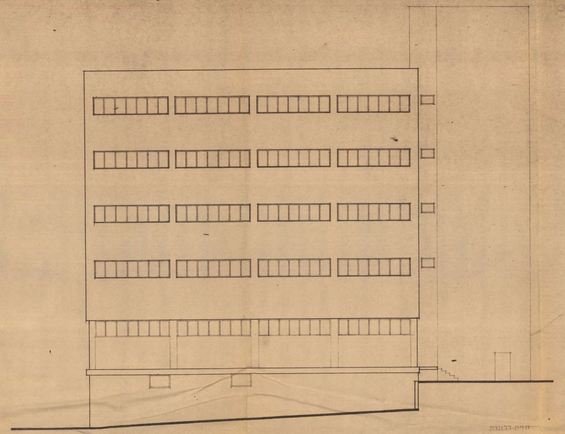

חזית דרומית

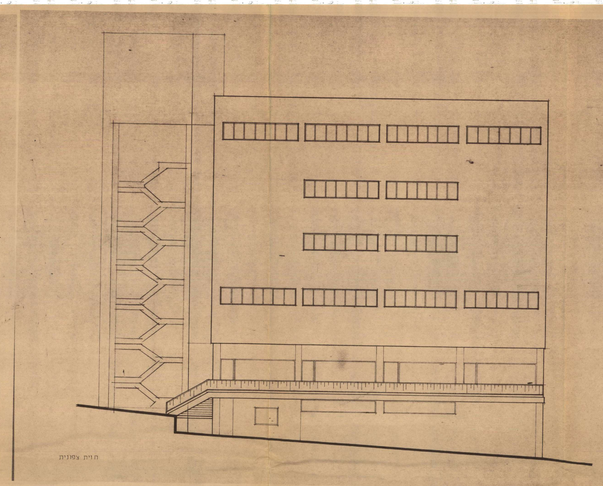

חזית צפונית

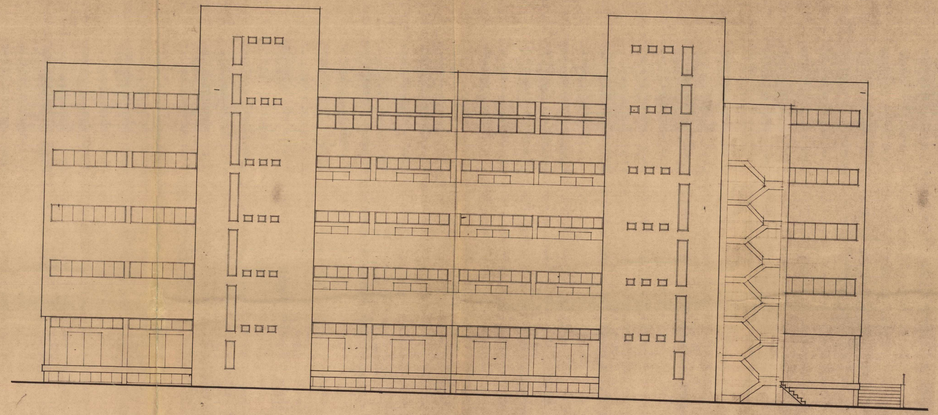
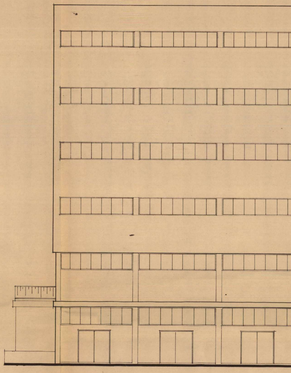
חזית מערבית